453/12361 पावती Original/Duplicate

Thursday,December 29 ,2016 नोंदणी क्रं. :39म

7:55 PM Regn.:39M

पावती क्रं.: 14931 दिनांक: 29/12/2016

गावाचे नाव: मुगांव

दस्तऐवजाचा अनुक्रमांक: मलस२-12361-2016

दस्तऐवजाचा प्रकार : खरेदीखत

सादर करणाऱ्याचे नाव: कॅलिडोस्कोप डेव्हलपर्स प्रा.लि.AAECK0069L तर्फे संचालक श्री.सारंग सुधाकर काळे तर्फे वि कु मु म्हणुन. विनायक नारायण परांजपे . .

नोंदणी फी	रु. 30000.00
दस्त हाताळणी फी	रु. 2900.00
डाटा एन्ट्री	रु. 20.00
पृष्ठांची संख्या: 145	
एकूण:	रु. 32920.00

आपणास मूळ दस्त ,थंबनेल प्रिंट,सूची-२ अंदाजे 8:12 PM ह्या वेळेस मिळेल.

MLS2

सह. दुय्यम निबंधक
श्रेणी-१, मुळशी-३

बाजार मुल्य: रु.50824550 /-

मोबदला रु.45000000/-

भरलेले मुद्रांक शुल्क : रु. 2550000/-

1) देयकाचा प्रकार: eChallan रक्कम: रु.30000/-

डीडी/धनादेश/पे ऑर्डर क्रमांक: MH007190543201617E दिनांक: 29/12/2016

बँकेचे नाव व पत्ता:

2) देयकाचा प्रकार: By Cash रक्कम: रु 2920/-

29/12/2016

सूची क्र.2

दुय्यम निबंधक : सह दु.नि. मुळशी-२
दस्त क्रमांक : 12361/2016
नोंदणी :
Regn:63m

गावाचे नाव : **1) भुगांव**

(1)विलेखाचा प्रकार	खरेदीखत
(2)मोबदला	45000000
(3) बाजारभाव(भाडेपटटयाच्या बाबतितपटटाकार आकारणी देतो की पटटेदार ते नमुद करावे)	50824550
(4) भू-मापन,पोटहिस्सा व घरक्रमांक (असल्यास)	1) पालिकेचे नाव:पुणे इतर वर्णन :, इतर माहिती: गाव मौजे भुगाव येथील सारंग सुधाकर काळे व राजेश सुधाकर काळे यांचे एकत्रीत मिळकती पुढील प्रमाणे. 1)स.नं.143 क्षेत्र 05 हे 58 आर पैकी 0 हे 14.47 आर, 2)स.नं.150/3 क्षेत्र 0 हे 6.9 आर पैकी 0 हे 2.3 आर, 3) स.नं.152/2 क्षेत्र 0 हे 10.6 आर पैकी 00 हे 3.54 आर,4)स.नं.154/2 क्षेत्र 0 हे 14 आर पैकी 00 हे 4.66 आर, 5)स.नं.156/6 क्षेत्र 0 हे 22.1 आर पैकी 00 हे 7.36 आर, 6)स.नं.197/16 क्षेत्र 0 हे 87 आर पैकी 00 हे 43.5 आर, सारंग सुधाकर काळे यांचे मिळकती पुढील प्रमाणे.7) स.नं.141/2 क्षेत्र 0 हे 9.4 आर पैकी 00 हे 00.13 आर, 8)स.नं.141/5 क्षेत्र 0 हे 3.8 आर पैकी 00 हे 0.06 आर, 9)स.नं.143 क्षेत्र 05 हे 58 आर पैकी 00 हे 7.73 आर, 10) स.नं.150/7 क्षेत्र 0 हे 3.3 आर पैकी 00 हे 1.1 आर,11)स.नं.154/6 क्षेत्र 01 हे 20 आर पैकी 00 हे 40 आर, 12)स.नं.155/4 क्षेत्र 0 हे 12.1 आर पैकी 00 हे 4.03 आर, 13)स.नं.155/6 क्षेत्र 0 हे 11.1 आर पैकी 00 हे 3.7 आर, 14)स.नं.156/5 क्षेत्र 0 हे 1.5 आर पैकी 0 हे 00.5 आर, 15)स.नं.159 क्षेत्र 0 हे 16 आर पैकी 00 हे 5.34 आर, 16)स.नं.197/6 क्षेत्र 0 हे 32 आर पैकी 00 हे 10.67 आर, 17)स.नं.197/29 क्षेत्र 0 हे 36 आर पैकी 00 हे 12 आर, येणेप्रमाणे 01 हे 61.09 आर या मिळकती मंजुर विशेष नगर विकास प्रकल्पासाठी प्रथम विक्री होत आहे.((Survey Number : 143 व इतर ;))
(5) क्षेत्रफळ	1) 0 हेक्टर , आर
(6)आकारणी किंवा जुडी देण्यात असेल तेव्हा.	
(7) दस्तऐवज करुन देणा-या/लिहून ठेवणा-या पक्षकाराचे नाव किंवा दिवाणी न्यायालयाचा हुकुमनामा किंवा आदेश असल्यास,प्रतिवादिचे नाव व पत्ता.	1): नाव:-श्री.सारंग सुधाकर काळे AFIPK7035C तर्फे वि कु मु म्हणुन. विनायक नारायण परांजपे . . वय:-49; पत्ता:-प्लॉट नं: ., माळा नं: ., इमारतीचे नाव: ., ब्लॉक नं: डेक्कन जिमखाना पुणे, रोड नं: ., महाराष्ट्र, पुणे. पिन कोड:-411004 पॅन नं:- 2): नाव:-श्री.राजेश सुधाकर काळे AJPPK1268C तर्फे वि कु मु म्हणुन. विनायक नारायण परांजपे . . वय:-49; पत्ता:-प्लॉट नं: ., माळा नं: ., इमारतीचे नाव: ., ब्लॉक नं: डेक्कन जिमखाना पुणे, रोड नं: ., महाराष्ट्र, पुणे. पिन कोड:-411004 पॅन नं:- 3): नाव:-मा.देणार. लुसिफर इंजिनिअरींग प्रा.लि.AAACL9805B तर्फे डायरेक्टर श्री.सारंग सुधाकर काळे तर्फे वि कु मु म्हणुन. विनायक नारायण परांजपे . . वय:-49; पत्ता:-प्लॉट नं: ., माळा नं: ., इमारतीचे नाव: ., ब्लॉक नं: डेक्कन जिमखाना पुणे, रोड नं: ., महाराष्ट्र, पुणे. पिन कोड:-411004 पॅन नं:-
(8)दस्तऐवज करुन घेणा-या पक्षकाराचे व किंवा दिवाणी न्यायालयाचा हुकुमनामा किंवा आदेश असल्यास,प्रतिवादिचे नाव व पत्ता	1): नाव:-कॅलिडोस्कोप डेव्हलपर्स प्रा.लि.AAECK0069L तर्फे संचालक श्री.सारंग सुधाकर काळे तर्फे वि कु मु म्हणुन. विनायक नारायण परांजपे . . वय:-49; पत्ता:-प्लॉट नं: ., माळा नं: ., इमारतीचे नाव: ., ब्लॉक नं: डेक्कन जिमखाना पुणे, रोड नं: ., महाराष्ट्र, पुणे. पिन कोड:-411004 पॅन नं:-
(9) दस्तऐवज करुन दिल्याचा दिनांक	29/12/2016
(10)दस्त नोंदणी केल्याचा दिनांक	29/12/2016
(11)अनुक्रमांक,खंड व पृष्ठ	12361/2016
(12)बाजारभावाप्रमाणे मुद्रांक शुल्क	2550000
(13)बाजारभावाप्रमाणे नोंदणी शुल्क	30000

iSarita v1.5.0

THE SEAL OF THE SUB-REGISTRAR OF दुय्यम निबंधक मुळशी-२ यांची मुद्रा मुळशी-२ MULSHI-2

(14)शेरा

मुल्यांकनासाठी विचारात घेतलेला तपशील:-:

मुद्रांक शुल्क आकारताना निवडलेला अनुच्छेद :- :

(ii) within the limits of any Municipal Council, Nagarpanchayat or Cantonment Area annexed to it, or any rural area within the limits of the Mumbai Metropolitan Region Development Authority or any other Urban area not mentioned in sub clause (i), or the Influence Areas as per the Annual Statement of Rates published under the Maharashtra Stamp (Determination of True Market Value of Property) Rules, 1995.

[illegible] वर हुकूम नक्कल

Sandip

सह दुय्यम निबंधक श्रेणी-१
मुळशी-२







म ल स - २

92369	9	9

२०९६

CHALLAN
MTR Form Number-6



GRN	MH007190543201617E	**BARCODE**		**Date** 29/12/2016-16:53:22	**Form ID** 25.1

Department	Inspector General Of Registration	**Payer Details**	
Type of Payment	Stamp Duty	**TAX ID (If Any)**	
	Registration Fee	**PAN No. (If Appliacable)**	AFIPK7035C
Office Name	MLS2_MULSHI 2 SUB REGISTRAR	**Full Name**	Sarang Kale
Location	PUNE		
Year	2016-2017 One Time	**Flat/Block No.**	Sr No. 143
Account Head Details	**Amount In Rs.**	**Premises/Building**	
0030046401 Stamp Duty	2250000.00	**Road/Street**	Bhugaon, Pune
0030063301 Registration Fee	30000.00	**Area/Locality**	01 H 61.09 R
		Town/City/District	
		PIN	4 1 2 1 1 5
		Remarks (If Any)	PAN2=AAECK0069L~SecondPartyName=Kaleidoscope Developers Pvt Ltd~CA=45000000
		Amount In Words	Twenty Two Lakh Eighty Thousand Rupees Only
Total	2280000.00		

Payment Details	BANK OF MAHARASHTRA	**FOR USE IN RECEIVING BANK**			
Cheque-DD Details		Bank CIN	REF No.	02300042016122985837	417168327
Cheque/DD No		Date		29/12/2016-16:52:48	
Name of Bank		Bank-Branch		BANK OF MAHARASHTRA	
Name of Branch		Scroll No. , Date		Not Verified with Scroll	

Mobile No. : 9970800674

म ल स - २ CHALLAN
MTR Form Number-6

9236	2	984
२०९६		

DEFACED FOR RS:2280000.00

THE SEAL OF THE SUB-REGISTRAR OF MULSHI-2

USER IGR045(MLS-2)

GRN	MH007190543201617E	BARCODE	DATE (IST) 29/12/2016	(IS)-459-12361 Date 29/12/2016-16:52:48	Form ID 25.1
Department	Inspector General Of Registration				
Type of Payment	Stamp Duty				

Sr No.	Deface Number	AMOUNT
1	0003980998201617	30000.00
2	0003980998201617	2250000.00

(Amt.in words) Registration Fee Twenty Two Lakh Eighty Thousand Rupees Only)

Office Name	MLS2_MULSHI 2 SUB REGISTRAR
Location	PUNE
Year	2016-2017 One Time

Account Head Details	Amount In Rs.
0030046401 Stamp Duty	2250000.00
0030063301 Registration Fee	30000.00
Total	2280000.00

Payer Details

TAX ID (If Any)	
PAN No. (If Appliacable)	AFIPK7035C
Full Name	Sarang Kale
Flat/Block No.	Sr No. 143
Premises/Building	
Road/Street	Bhugaon, Pune
Area/Locality	01 H 61.09 R
Town/City/District	
PIN	4 1 2 1 1 5

Remarks (If Any)

PAN2=AAECK0069L~SecondPartyName=Kaleidoscope Developers Pvt Ltd~CA=45000000

Amount In Words	Twenty Two Lakh Eighty Thousand Rupees Only

Payment Details	BANK OF MAHARASHTRA

FOR USE IN RECEIVING BANK

Cheque-DD Details		Bank CIN	REF No.		
		02300042016122985837	417168327		
Cheque/DD No		Date	29/12/2016-16:52:48		
Name of Bank		Bank-Branch	BANK OF MAHARASHTRA		
Name of Branch		Scroll No. , Date	Not Verified with Scroll		

Mobile No. : 9970800674


म ल स - २

9239 | 3 | 389

२०१६

CHALLAN

MTR Form Number-6



GRN	MH007193553201617E	BARCODE		Date	29/12/2016-17:40:36	Form ID	25.1

Department	Inspector General Of Registration	**Payer Details**	
Type of Payment	Non-Judicial Customer-Direct Payment	**TAX ID (If Any)**	
	Sale of Non Judicial Stamps IGR Rest of Maha	**PAN No. (If Appliacable)**	AFIPK7035C
Office Name	MLS2_MULSHI 2 SUB REGISTRAR	**Full Name**	Sarang Kale
Location	PUNE		
Year	2016-2017 One Time	**Flat/Block No.**	Sr No.143
Account Head Details	**Amount In Rs.**	**Premises/Building**	
0030046401 Sale of NonJudicial Stamp	300000.00	**Road/Street**	01 H 61.09 R
		Area/Locality	Bhugaon, Pune
		Town/City/District	
		PIN	4 1 2 1 1 5
		Remarks (If Any)	PAN2=AAECK0069L~PN=Kaleidoscope Developers Pvt Ltd~CA=6000000
		Amount In Words	Three Lakh Rupees Only
Total	300000.00		

Payment Details	BANK OF MAHARASHTRA	**FOR USE IN RECEIVING BANK**			
Cheque-DD Details		Bank CIN	REF No.	02300042016122986104	417201314
Cheque/DD No		Date		29/12/2016-17:39:27	
Name of Bank		Bank-Branch		BANK OF MAHARASHTRA	
Name of Branch		Scroll No. , Date		Not Verified with Scroll	

Mobile No. : 9970800674

CHALLAN

MTR Form Number-6

म ल स - २

923E9 | २ | १४५

DEFACED FOR RS:300000.00

USER

IGR045(MLS-2)

GRN	MH007193652016[illegible]	BANK CODE	[illegible]	Date	29/12/2016-17:40:36	**Form ID**	25.1

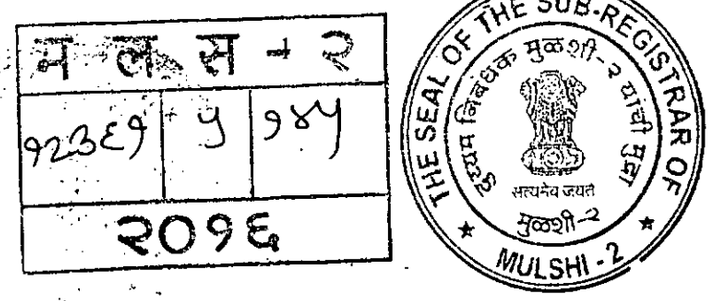
Department	Inspector General Of Registration	**Payer Details**	
Type of Payment	Non-Judicial Customers Indirect Payment	**TAX ID (If Any)**	
	Sale of Non Judicial Stamps IGR Rest of Maha	**PAN No. (If Applicable)**	AFIPK7035C
Office Name	MLS2_MULSHI 2 SUB REGISTRAR	**Full Name**	Sarang Kale
Location	PUNE		
Year	2016-2017 One Time	**Flat/Block No.**	Sr No.143
Account Head Details	**Amount In Rs.**	**Premises/Building**	
0030046401 Sale of NonJudicial Stamp	300000.00	**Road/Street**	01 H 61.09 R
		Area/Locality	Bhugaon, Pune
		Town/City/District	
		PIN	4 1 2 1 1 5
		Remarks (If Any)	PAN2=AAECK0069L~PN=Kaleidoscope Developers Pvt Ltd~CA=6000000
		Amount In Words	Three Lakh Rupees Only
Total	300000.00		

Payment Details	BANK OF MAHARASHTRA	**FOR USE IN RECEIVING BANK**			
Cheque-DD Details		Bank CIN	REF No.	02300042016122986104	417201314
Cheque/DD No		Date		29/12/2016-17:39:27	
Name of Bank		Bank-Branch		BANK OF MAHARASHTRA	
Name of Branch		Scroll No. , Date		Not Verified with Scroll	

Mobile No. : 9970800674

Sr No. 1 Deface Number 00039809992016[illegible] AMOUNT 300000.00 29/12/2016

(Amt.in words:Three Lakh Rupees Only)



DEED OF CONVEYANCE

THIS INDENTURE MADE AT PUNE ON THIS 29th DAY OF December OF IN THE YEAR 2016.

BETWEEN

(1) SHRI SARANG SUDHAKAR KALE, (PAN AFIPK 7035 C), age 52 years, occupation: Agriculture and Business,

(2) SHRI RAJESH SUDHAKAR KALE, (PAN AJPPK 1268 C), age 54 years, occupation: Agriculture and Business,

Both residing at Deccan Gymkhana, Pune – 411 004.

Hereinafter referred to as **'THE VENDORS'** (which expression shall unless repugnant to the context meaning thereof mean and include the Vendors themselves, their legal heirs, administrators, executors, attorneys, assigns etc.)

'THE PARTY OF THE FIRST PART'

AND

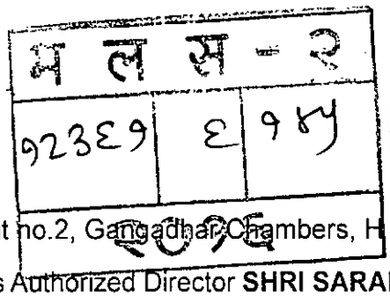
KALEIDOSCOPE DEVELOPERS PVT. LTD., (PAN AAECK 0069 L) a Private Limited Company registered under the Provisions of Indian Companies Act, 1956 having its registered office at 701, Rajyog CHS, Shivaji Park, Sakharam Keer Marg, Mahim, Mumbai – 400016 through its Authorized Director **SHRI SARANG SUDHAKAR KALE,** age about 52 Years, occupation : business and Agriculturist.

Hereinafter referred to as **'THE PURCHASER'** (which expression shall unless, repugnant to the context or meaning thereof, mean and include the present and future Directors, successors, survivors, legal representatives, attorneys, administrators, liquidators, executors and assigns)

'THE PARTY OF THE SECOND PART'

AND

LUCIFER ENGINEERING PVT. LTD., (PAN AAACL 9805 B) a Private Limited Company registered under the Provisions of Indian Companies Act, 1956 having





its registered office at Flat no.2, Gangadhar Chambers, H No. 314, Narayan Peth, Pune 411030 through its Authorized Director **SHRI SARANG SUDHAKAR KALE,** age about 52 Years, occupation : business and Agriculturist residing at Pune – 411 004.

Hereinafter referred to as **"THE CONSENTING PARTY"** (which expression shall unless, repugnant to the context or meaning thereof, mean and include the present and future Directors, successors, survivors, legal representatives, administrators, liquidators, attorneys, executors and assigns)


PARTY OF THE THIRD PART

WHEREAS:

01) All that piece and parcel of lands totally admeasuring about 01 Hectare 61.09 Ares i.e. 4.027 Acres (Approx.) situated at Village: Bhugaon, Tal. Mulshi, Dist. Pune within the registration District of Pune, Sub Registration District, Taluka: Mulshi, within the limits of Tahsil Mulshi (Paud) and Zilla Parishad, Pune, Taluka Panchayat Samiti, Mulshi (which are more particularly described in the **SCHEDULE** written hereunder and hereinafter referred to as the **'SAID PROPERTY'**) are owned by the Vendors.

02) The said Property is within the Agricultural Zone and outside the Pune Urban Agglomeration Limits of Pune City. The 7/12 extracts of the said Property are annexed hereto as **ANNEXURE "A-1 to A-33"**. Some of the properties out of the said properties have been purchased by the Vendors but effect of the mutation entries have not been given on the respective 7/12 Extracts. The Vendors have attached the Index II of their Sale Deeds to these presents as **ANNEXURE B 1** to **B 6**. The Vendors hereby declare that they have not sold any of the land to any one and their holding is as per the said Index II Extracts. The Zone Certificate to that effect is annexed hereto and marked as **ANNEXURE " C "**.

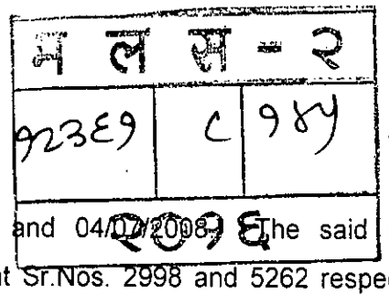
03) Some of previous Owners 1) Shri. Vishwas Vijay Bhisey, 2) Shri. Vijay Moreshwar Bhisey, 3) Mrs. Namrata Datt and 4) Shri. Kailas Shankar Kamble had executed a Development Agreement and Power of Attorney both dated 22-1-2007 for the several lands totally admeasuring 21 H. 83.89 Are including the said property in favour of the Consenting Party. The said Development Agreement and Power of Attorney are registered at Sr. Nos.503 and 504 on even date at the office of Sub Registrar, Paud



(Mulshi), Dist. Pune. Thereafter the said previous owners 1) Shri. Vishwas Vijay Bhisey, 2) Shri. Vijay Moreshwar Bhisey, 3) Mrs. Namrata Datt and 4) Shri. Kailas Shankar Kamble have executed 2 Deeds of Correction cum Supplementary Agreements dated 15-12-2007 and 11-11-2008 in favour of the Consenting Party. The said Deeds of Correction are registered at Sr. No.8609/2007 and 8265/2008 on their respective dates at the office of Sub Registrar, Mulshi (Paud).

04) The Consenting Party had obtained the development rights of the lands totally admeasuring 21 H. 83.89 Are including the said property for the purposes of promoting a Special Township Project (S.T.P.). The Consenting Party was also in the process of purchasing the several other properties in the vicinity of the lands under the Development Agreement. , However, subsequently the Consenting Party proposed to purchase the lands through their agents i.e. the Vendors herein.

05) The Consenting Party as per the terms of the said Development Agreement was authorized to get the Sale Deed / Final Deed of Conveyance executed from the previous owners in the name of their nominees and accordingly directed the previous owners to execute two separate Deeds of Conveyance, one in favour of the Vendor No. 1 and the other one in the name of both the Vendors herein for lands totally admeasuring 21 H. 83.89 Are including the said property. The Vendor No. 1 herein therefore purchased from the said previous owners the lands admeasuring 01 Hector 69.25 Aar out of the lands admeasuring 21 H. 83.89 Are under Development Agreement and additional area admeasuring 01 Hector 69.845 Aar including some of the said property totaling to lands admeasuring 03 Hectors 39.095 Aar by way of one joint Deed of Conveyance dated 4/10/2007. The said Deed of Conveyance is registered at Sr. No. 6786/2007 on even date at the office of Sub Registrar, Mulshi (Paud). The name of Vendor No. 1 has been mutated on the 7/12 extracts of the lands admeasuring 03 Hectors 39.095 Aar including some of the said property by way of Mutation Entry No. 6107 dated 26/10/2007 Thereafter the Vendors herein therefore purchased the lands admeasuring 18 Hectors 86.59 Aar out of the lands admeasuring 21 H. 83.89 Are out of the said property by way of the Deed of Conveyance dated 14/10/2009. The said Deed of Conveyance is registered at Sr.No. 5899 on even date at the office of Sub Registrar, Mulshi (Paud). Thereafter the Vendor No. 1 herein purchased some of the lands out of the said property by way of two Deeds of Conveyance dated

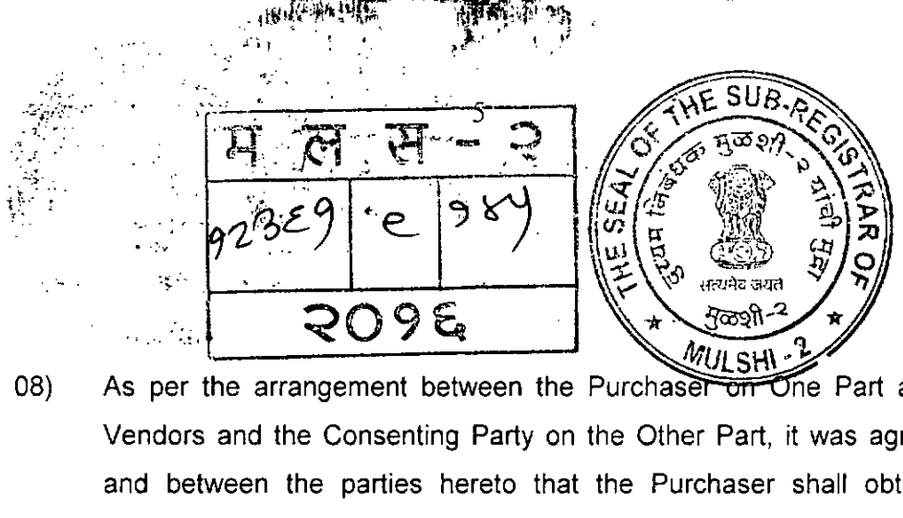




16/04/2008 and 04/07/2008. The said Deeds of Conveyance are registered at Sr.Nos. 2998 and 5262 respectively on even dates at the office of Sub Registrar, Mulshi (Paud). The names of Vendors have been mutated on the 7/12 extracts of the lands admeasuring 18 Hectors 86.59 Aar by way of Mutation Entry No. 6660 dated 21/11/2009.

06) The Consenting Party, through its agents i.e. Vendors, has acquired lands out of the said property from time to time directly from the original owners by way of Sale Deeds. Due to the lack of funds, it was not possible for the Consenting Party to continue with the proposed acquisition of lands. Therefore the Consenting Party approached IL & FS Financial Services Limited (said "IL & FS ") for the project loan. The said IL & FS advanced loan to the Consenting Party and the Consenting Party, through its agents i.e. Vendors, has further bought the lands out of the said property. Due to the financial stringencies, the Consenting Party was not in a position to repay the said loan and therefore approached the Purchaser herein. The Purchaser was looking for an unbroken and continuous piece of land in which hill top/hill slope zone does not exceed 40% of the total land. After the negotiations between the Purchaser and the Consenting Party, it was agreed by and between the parties hereto that the Purchaser would provide a finance to the Consenting Party for the purchase of lands out of the said property and the Consenting Party using the said finance shall purchase the lands out of the said property in the names of the Vendors for and on behalf of the Consenting Party. It was further agreed between the Consenting Party and the Purchaser that as and when the acquisition of the said property is completed by the Consenting Party, the Vendors and Consenting Party shall sell / transfer / assign the said property to the Purchaser by executing a Final Deed of Conveyance. The Board of Directors of the Consenting Party and the Purchaser have passed necessary respective separate resolutions from time to time to corroborate the said arrangement between themselves.


07) The Consenting Party, in the name of and through the Vendors, acquired the said property now fully. The Purchaser has advanced the finance of Rs. 4,50,00,000/- (Rupees Four Crores Fifty Lacs only) to the Consenting Party till date and the said advances are still outstanding against the Consenting Party. The Consenting Party has paid the considerations to the various original owners under the Sale Deeds by using the said finance from the Purchaser and the Vendors got the various Sale Deeds executed from the original owners.



08) As per the arrangement between the Purchaser on One Part and the Vendors and the Consenting Party on the Other Part, it was agreed by and between the parties hereto that the Purchaser shall obtain the permission for promoting a Special Township Project on the said property and the Consenting Party alongwith Vendors and other Owners shall co-operate with the Purchaser.

09) The Purchaser and Shri. Rajesh Sudhakar Kale, Sudhakar Gangadhar Kale made an application dated and 24th January, 2013 and 17th April, 2015 to the Government for developing the said property as Special Integrated Township Project and thus under the provisions of sub-section 3 of Section 18 of the Maharashtra Regional and Town Planning Act, 1966 for grant of Locational Clearance in respect of the lands admeasuring 41 Hectares 90.34 Aars equivalent to 104.758 Acres approximately in village Bhugaon, Tal. Mulshi, District Pune. The said Property is described in the schedule and the same forms the part of the aforesaid approximate 41 Hectares 90.34 Aars equivalent to 104.758 Acres land being the said property. By a notification dated 2nd July, 2015 bearing Reference No. TPS 1814/2130/CR-98/15/UD-13 issued by the Urban Development Department, Mantralaya, the State Government accorded Locational Clearance to the said property for the purpose of developing the same as a Special Township Project, subject to the terms and conditions stated therein. By a No Objection Certificate 18th January, 2014 bearing reference no. 10 of 2014, the Talathi, Bhugaon confirmed that the said properties do not belong to members of Adivasi community. By a letter dated 12th September, 2014 bearing Reference No. Ku.Ka/Ka.Vi/306/2014 the Tahasildar, Mulshi, has confirmed that the said properties do not belong to the members of Adivasi community. By a letter dated 6th September, 2014 and 29th December 2015 bearing Reference No. Mu.Aa/Ka-2/ Prasha 6/Vinav/(241/25)/5186/2014 and No. Mu.Aa/Ka-2/ Prasha 6/Vinav/(241/23)/6240/2015 the Maharashtra Water Department, has granted its No Objection for construction of the proposed township on the said property. By a No Objection Certificate dated 28th July, 2014 bearing Reference No. Mauvim/Pra.Aa.Pune-2/2051/2014, the Maharashtra Industrial Development Corporation, stated that the Maharashtra Development Industrial Corporation have no interest in the said property. By a No Objection Certificate dated 1st October, 2012 bearing reference no. 345 of 2012, the Grampanchayat, Bhugaon, has granted it's no objection for drawing water from Mutha River for the Special Township Project. By a No Objection Certificate dated 9th

म त स - २
९२३६९ | ९० | ९४
२०१६



September, 2014 bearing reference no. SE/EHV/O&M/Circle/PM/T-53/2665, the Superintendent Engineer, Maharashtra State Electricity Transmission Company Limited, confirmed that no EHV Line passes through the said properties and thus has no objection certificate to undertake construction on the said property. By a No Objection Certificate dated 11th January, 2013 bearing reference no. 278 of 2013, the Executing Engineer, Maharashtra State Electricity Transmission Company Limited, confirmed that High Tension Line does not pass through the said property. By a No Objection Certificate dated 3rd September, 2014 bearing reference no. Tantra/Naharkat/2014/2105 the Director, Archeological Museum Department, granted it's No Objection for carrying out construction on the said property. By a No Objection Certificate dated 8th January, 2013 bearing reference no. A/LAND/38/676/2012-13 and 19th April, 2013 bearing Reference No. A/LAND/38/61/2013-14 the Forest Conservation Officer (Laws regarding to Private, conservatives and etc.), has certified that the said Property is not private, reserved or conserved forest land. The Pune Metropolitan Regional Development Authority (PMRDA) has issued Letter of Intent (LOI) dated 9th March 2016 bearing Reference No. PMRDA/Mou. Bhugaon/S.no.125/5 & etc/1975 in favour of the Purchaser. All the above mentioned Notifications, Permissions, NOCs and LOI are annexed hereto as **ANNEXURE _____ to ANNEXURE _____**.

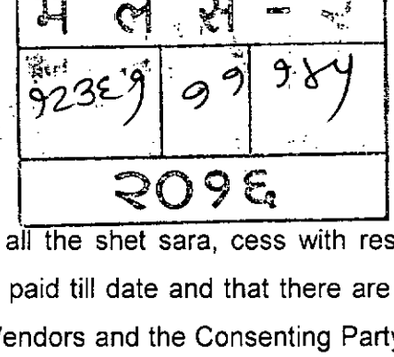
10) The Vendors and the Consenting Party have represented to the Purchaser as under :


a) That the said Property has been acquired by them for and on behalf of the Consenting Party.

b) That there exists no dispute or any pending litigation with respect to the said Property.

c) That there exists no boundary dispute with any of the adjoining owners.

d) That they have not created any charge in favour of any person/party or any other financial institution with respect to the said Property, except the creation of Mortgage in favour of IL & FS.





e) That all the shet sara, cess with respect to the said Property have been paid till date and that there are no arrears due and payable by the Vendors and the Consenting Party and that they shall ensure that all such dues are paid and if the same are found unpaid then that shall be obligation of the Vendors and the Consenting Party to pay the same.

f) That the Vendors and the Consenting Party have been in absolute possession of the said Property.


g) That the Vendors and the Consenting Party have not granted any easementary rights over the said Property in favour of any person/party.

11) The Vendors and the Consenting Party have assured the Purchaser that there is no impediment to the present transaction under any Law subsisting at present.

12) The Vendors and the Consenting Party assure that all/any title related matters shall continue to be their responsibility and the same shall be cleared by them at their own costs and expenses and the Purchaser shall not be held liable or responsible for the same. The Vendors and the Consenting Party agree to indemnify and keep the Purchaser indemnified for and in respect of the same.

13) As per the said arrangement between the Vendors, Consenting Party and the Purchaser, the Purchaser has agreed to purchase the said Property for the consideration of Rs. 4,50,00,000/- (Rupees Four Crores Fifty Lacs only) as mentioned herein below. The Vendors and the Consenting Party have accepted and agreed to sell the said Property to the Purchaser for the abovementioned consideration being highest and as per the prevailing market rate. The Purchaser has agreed to purchase and the Vendors and the Consenting Party have agreed to sell the said Property on the terms and conditions mutually agreed between them.

NOW THIS INDENTURE WITNESSETH that in pursuance of the said agreement and in consideration of a sum of Rs. 4,50,00,000/- (Rupees Four Crores Fifty Lacs only) paid by Purchaser to the Vendors through Consenting Party as a finance for purchase of the some of the lands out of the said property at that time and the said amount of finance has been






converted by the parties hereto in the form of the consideration of the said property received from the Purchaser by the Vendors through Consenting Party and the Purchaser hereby discharges the Consenting Party from repayment of the said loan amount / finance forever. It is agreed between the parties hereto that the Vendors and the Consenting Party have no liability to repay the said loan to the Purchaser since it is converted into the part of the consideration of the said property.

The payment and receipt whereof the Vendors doth hereby admit and acknowledge and forever discharge the Purchaser. The Purchaser has paid Rs. 4,50,00,000/- (Rupees Four Crores Fifty Lacs only) to the Consenting Party as mentioned hereinabove (The payment and receipt whereof the Consenting Party doth hereby admit and acknowledge and forever discharges the Purchaser). The consenting party has sold/ transferred / assigned all its rights in the said property in favour of the Purchaser. The consenting party assures the Purchaser that it has not created any third party interest, charge, mortgage (except the mortgage as mentioned hereinabove), or any other encumbrance of whatsoever nature on the said property. The Vendors doth hereby grant, sell, convey, transfer and assure unto the Purchaser the said Property, (more particularly described in the **SCHEDULE** written hereunder) **together with** all privileges, easements and appurtenances belonging thereto **and together with** all and singular, yards, area, compounds, ditches, fences, trees, drains, ways, paths, passages, common gullies, wells, waters and water courses, plants lights, liberties, privileges, easements, profits, advantages, rights, members and appurtenances whatsoever to the said property or any part thereof belonging or in any wise appertaining or with the same or any part thereof now at any time heretofore usually held, sued, occupied or enjoyed or reputed or known as part or member thereof and to belong or be appurtenant thereto **and also together with** all the deeds, documents, writings, vouchers and other evidences of title related to the said property or ground, hereditaments and property, possession, benefit, claim and demand and whatsoever at law and in equity of the Vendors into out of or upon the said Property or any part thereof **to have and to hold** all and singular and said Property hereby granted, released, conveyed and assured and intended or expressed so to be with it and every of its rights, members and appurtenances (all which are hereinafter for the sake of brevity referred to as **"the said Property"**) unto and to the use and benefit of the Purchaser absolutely and forever **subject** to the payment of all rents, rates, taxes and cess, assessments, dues and


म ल स - २

9239	93	984
२०९६		



duties now chargeable upon the same or hereafter to become payable to the Government or to the Gram Panchayat or any other public body in respect thereof **and** The Vendors doth hereby for themselves and their legal heirs, executors and administrators covenant with the Purchaser **that** notwithstanding any act, deed, matter or thing whatsoever by the Vendors or any person or persons lawfully or equitably claiming by, from through under or in trust for them made, done, committed, omitted or knowingly or willingly suffered to the contrary **the Vendors** have now in themselves good right, full power and absolute authority to grant, convey, transfer and assure the said property hereby granted conveyed, transferred and assured or intended so to be unto and to the use of the Purchaser in the manner aforesaid **and that** it shall be lawful for the Purchaser in the manner aforesaid **and that** it shall be lawful for the Purchaser at all times hereafter to peaceably and quietly to hold, enter upon, have occupy, possess and enjoy the said Property hereby granted with their appurtenances and receive the rents, issues and profits thereof and every part thereof and for its own use and benefit without any suit lawful eviction, interruption, claim and demand whatsoever from or by the Vendors or by any person/persons lawfully or equitably claiming or to claim by, from under or in trust for them or any one of them and that free and clear and freely and clearly and absolutely, exonerated, released and forever discharged or otherwise by the Vendors will and sufficiently saved, defended kept harmless and indemnified of from and against all former and other estates, titles, charges and encumbrances whatsoever either already or by any other person or persons lawfully or equitably claiming or to claim by, from, under or in trust from them or any one of them and further that they, the Vendors and all persons having or lawfully or equitably claiming any estate, right title or interest at law or in equity in the said Property hereby granted or any part thereof by from under or in trust for the Vendors or their legal heirs, executors and administrators shall and will from time to time and at all times hereafter at the request and costs of the Purchaser do and execute or cause to be done and executed all such further and other lawful and reasonable acts, deeds, things, matters conveyances and assurances in law whatsoever for the better, further and more perfectly and absolutely granting the said Property unto and the use of the Purchaser in the manner aforesaid as shall or may be reasonably required by the Purchaser, its successors in interest and assigns or its counsel in law and assuring that the said Property and every part thereof hereby granted unto and to the use of the

म ल श - २
२३९ | ९४ | ९५
२०१८



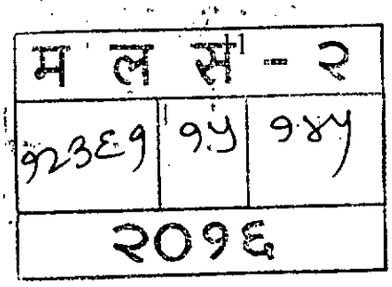
Purchaser, its successors in interest and assigns and shall be reasonably required.


AND in consideration aforesaid the Vendors doth grant unto the Purchaser its successors in interest and assigns and the person or persons owing, occupying and possessing the said property and its visitors, agents, servants at all times and from time to time by night and by day to pass and re-pass over and across the internal roads or passages leading to the said Property by foot, or by any vehicle of whatsoever nature to hold the same unto the Purchaser, its successors in interest and assigns and the person owing, occupying and possessing the said Property and that the right of way shall be appurtenant and annexed to the said Property and shall run with the same.

AND the Vendors in consideration aforesaid doth also grant to the Purchaser its successors in interest and assigns the benefits of all the common amenities, easements that may be provided to the said Property and other amenities

AND THIS DEED STILL FURTHER WITNESSETH that the Purchaser confirm having received clear vacant and peaceful and absolute possession of the said Property from the Vendors on the execution hereof.

AND THE VENDORS in consideration aforesaid doth hereby covenant with the Purchaser that the Vendors shall and will unless prevented by fire or some other inevitable or unavoidable accident, from time to time and at all times hereafter upon every reasonable request and at the cost of the Purchaser or any person or persons having or lawfully claiming through under or in trust for the Purchaser, its successors in interest and assigns produce or cause to be produced to it or its agents or lawyers or at any legal hearing, commission or examination or otherwise as occasion shall require, all or any of the deeds and writings for the purpose of showing the Purchaser's title to the said property hereby conveyed and will permit the same to be examined, inspected or given in evidence and will at the like request and cost of the Purchaser or any such other person or persons as aforesaid deliver or cause to be delivered to it such other person or persons as aforesaid deliver or cause to be delivered to it such attested or other copies or abstracts or extracts from the said deeds and writings or any of them as it may require and shall in the meantime,





unless prevented as aforesaid keep them safe, unobliterated or uncancelled.

THIS DEED STILL FURTHER WITNESSETH THAT as per the provisions of Section 63 - 1 A of Maharashtra Tenancy and Agricultural Lands Act the Purchaser Company is purchasing / acquiring the Agricultural Lands by these presents for the purpose of Integrated Township Project and as such no prior permission of the Collector is required.

THIS DEED STILL FURTHER WITNESSETH that the stamp duty registration charges and other charges incidental thereto, payable on this document are being borne and paid by the Purchaser alone.

LOCATION: The said Property is situated in Division 6 of the Government ready recknor kept of the office of Sub Registrar, Mulshi (Paud) under the heading 'Jirayati Land'. The said property is under proposed Integrated Township Project and therefore eligible for various concessions provided in the valuation rules.

VALUATION: The consideration for the present transaction is Rs. 4,50,00,000/- (Rupees Four Crores Fifty Lacs only) which is more than the value of ready recknor of Rs. 5,08,24,550 /- and as such the Purchasers have paid Stamp Duty of Rs. 25,50,000 /- on the higher valuation. The registration charges of Rs.30,000/- are paid separately.

THE SCHEDULE ABOVE REFERRED TO :

The lands situate at Village Bhugaon, within the limits of the Sub Registrar of Sub Division and Taluka Mulshi (Paud), Panchayat Samiti Mulshi, Division, District and Zilla Parishad Pune.

LAND JOINTLY OWNED BY SARANG SUDHAKAR KALE (VENDOR 1) AND RAJESH SUDHAKAR KALE (VENDOR 2)

1) All that piece and parcel of land bearing Survey no. 143, admeasuring about 00 Hectares 14.47 Aar out of total area of 5 Hectares 56 Aars having assessment value at Rs. 6-50 paise.

On or Towards EAST	S.No	:- 136,141 &142
On or Towards SOUTH	S.No	:- 130

म ल म - २
१२३९ | ९६ | ९४

On or Towards WEST S.No :-~~146~~
On or Towards NORTH S.No :- 146 &154

2) All that piece and parcel of land bearing Survey no. 150/3, admeasuring about 00 Hectares 2.3 Aar out of total area of 00 Hectares 6.9 Aars having assessment value at Rs.00-44 paise.

On or Towards EAST S.No :- 154
On or Towards SOUTH S.No :- 154 & 142
On or Towards WEST S.No :- 154,149 & 148
On or Towards NORTH S.No :- 154

3) All that piece and parcel of land bearing Survey no. 152/2, admeasuring about 00 Hectares 3.54 Aar out of total area of 00 Hectares 10.6 Aars having assessment value at Rs.00-47 paise.

On or Towards EAST S.No :- 154 & 153
On or Towards SOUTH S.No :- 154 & 151
On or Towards WEST S.No :- 146
On or Towards NORTH S.No :- 154

4) All that piece and parcel of land bearing Survey no. 154/2, admeasuring about 00 Hectares 4.66 Aar out of total area of 00 Hectares 14 Aars having assessment value at Rs.00-16 paise.

On or Towards EAST S.No :- 155 & 156
On or Towards SOUTH S.No :- 156 & 150
On or Towards WEST S.No :- 146, 148 &149
On or Towards NORTH S.No :- 144

5) All that piece and parcel of land bearing Survey no. 156/6, admeasuring about 00 Hectares 7.36 Aar out of total area of 00 Hectares 22.1 Aars having assessment value at Rs.1-45 paise.

On or Towards EAST S.No :- 159
On or Towards SOUTH S.No :- 142
On or Towards WEST S.No :- 150 &154
On or Towards NORTH S.No :- 155

म ल स - २
२३६९ | ९७ | ९४
२०१६

THE SEAL OF THE SUB-REGISTRAR OF मुख्यनिबंधक मुळशी-२ यांची मुद्रा सत्यमेव जयते मुळशी-२ MULSHI-2

6) All that piece and parcel of land bearing Survey no. admeasuring about 00 Hectares 43.5 Aar out of total area of 00 Hectares 87 Aars having assessment value at Rs.00-59 paise.

On or Towards EAST	S.No	:- 187, 188, 189, 191, 195 & 196
On or Towards SOUTH	S.No	:- 198
On or Towards WEST	S.No	:- 126, 127, 128, 129, 131, 132, 134, 135 & 137
On or Towards NORTH	S.No	:- 137 & 138

LAND OWNED BY SARANG SUDHAKAR KALE (VENDOR 1)

7) All that piece and parcel of land bearing Survey no. 141/2, admeasuring about 00 Hectares 00.13 Aar out of total area of 00 Hectares 9.4 Aars having assessment value at Rs.00-56 paise.

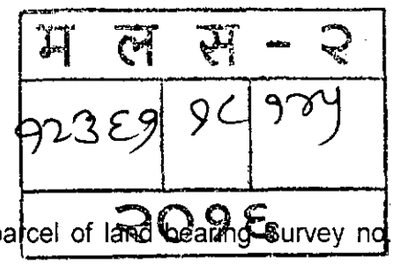
On or Towards EAST	S.No	:- 140
On or Towards SOUTH	S.No	:- 136, 143
On or Towards WEST	S.No	:- 143
On or Towards NORTH	S.No	:- 142

8) All that piece and parcel of land bearing Survey no. 141/5, admeasuring about 00 Hectares 0.06 Aar (i.e 6 sq.mtr.) out of total area of 00 Hectares 3.8 Aars having assessment value at Rs.00-12 paise.

On or Towards EAST	S.No	:- 140
On or Towards SOUTH	S.No	:- 136, 135
On or Towards WEST	S.No	:- 143
On or Towards NORTH	S.No	:- 142, 159

9) All that piece and parcel of land bearing Survey no. 143, admeasuring about 00 Hectares 7.73 Aar out of total area of 5 Hectares 56 Aars having assessment value at Rs. 6-50 paise.

On or Towards EAST	S.No	:- 136,141 &142
On or Towards SOUTH	S.No	:- 130
On or Towards WEST	S.No	:- 144
On or Towards NORTH	S.No	:- 146 &154





10) All that piece and parcel of land bearing Survey no. 150/7, admeasuring about 00 Hectares 1.1 Aar out of total area of 00 Hectares 3.3 Aars having assessment value at Rs. 00-16 paise.

On or Towards EAST	S.No	:- 154/12, 154/13
On or Towards SOUTH	S.No	:- 142/1, 155/1
On or Towards WEST	S.No	:- 143
On or Towards NORTH	S.No	:- 150/6

11) All that piece and parcel of land bearing Survey no. 154/6, admeasuring about 00 Hectares 40 Aar out of total area of 01 Hectares 20 Aars having assessment value at Rs. 1-25 paise.

On or Towards EAST	S.No	:- 154/7, 156/7, 156/6,156/1 to 4
On or Towards SOUTH	S.No.	: -154/7, 154/12, 154/13
On or Towards WEST	S.No.	: -154/6 part, 154/10, 154/11
On or Towards NORTH	S.No.	:- 144


12) All that piece and parcel of land bearing Survey no. 155/4, admeasuring about 00 Hectares 4.03 Aar out of total area of 00 Hectares 12.1 Aars having assessment value at Rs. 00-66 paise.

On or Towards EAST	S.No	:- 157
On or Towards SOUTH	S.No	:- 155/2
On or Towards WEST	S.No	:- 155 remaining part
On or Towards NORTH	S.No	:- 155/5

13) All that piece and parcel of land bearing Survey no. 155/6, admeasuring about 00 Hectares 3.7 Aar out of total area of 00 Hectares 11.1 Aars having assessment value at Rs. 00-66 paise.

On or Towards EAST	S.No	:- 157
On or Towards SOUTH	S.No	:- 155/5
On or Towards WEST	S.No	:- 155/7
On or Towards NORTH	S.No	:- 155/7, 155 remaining part

14) All that piece and parcel of land bearing Survey no. 156/5, admeasuring about 00 Hectares 00.5 Aar out of total area of 00 Hectares 1.5 Aars having assessment value at Rs. 00-00 paise.



On or Towards EAST	S.No	:- 157, 159
On or Towards SOUTH	S.No	:- 156/6
On or Towards WEST	S.No	:- 156/5 remaining part
On or Towards NORTH	S.No	:- 156/4

15) All that piece and parcel of land bearing Survey no. 159, admeasuring about 00 Hectares 5.34 Aar out of total area of 00 Hectares 16 Aars having assessment value at Rs. 00-14 paise.

On or Towards EAST	S.No	:- 157
On or Towards SOUTH	S.No	:- 157
On or Towards WEST	S.No	:- 156/6, 156 remaining part
On or Towards NORTH	S.No	:- 157, 159 remaining part

16) All that piece and parcel of land bearing Survey no. 197/6, admeasuring about 00 Hectares 10.67 Aar out of total area of 00 Hectares 32 Aars having assessment value at Rs. 1-25 paise.

On or Towards EAST	S.No	:- 197
On or Towards SOUTH	S.No	:- 197 remaining part, 197/7
On or Towards WEST	S.No	:- 131
On or Towards NORTH	S.No	:- 197/5

17) All that piece and parcel of land bearing Survey no. 197/29, admeasuring about 00 Hectares 12 Aar out of total area of 00 Hectares 36 Aars having assessment value at Rs. 00-41 paise.

On or Towards EAST	S.No	:- 198/29, 197/30
On or Towards SOUTH	S.No	:- 198
On or Towards WEST	S.No	:- 197/28
On or Towards NORTH	S.No	:- 197/24, 197/27

The total area of the land being transferred / sold by these presents is **01 hectares 61.09 Aars.**

म ल स - २		
२३६९	२०१४	

THE SEAL OF THE SUB-REGISTRAR OF दुय्यम निबंधक मुळशी-२ यांची मुद्रा सत्यमेव जयते MULSHI-2

IN WITNESS WHEREOF THE PARTIES HERETO HAVE HEREUNTO SET AND SUBSCRIBED THEIR RESPECTIVE HANDS AND SEAL THE DAY AND YEAR FIRST HRERINABOVE WRITTEN.





T.I.

SHRI SARANG SUDHAKAR KALE





T.I.

SHRI RAJESH SUDHAKAR KALE

'THE VENDORS'

KALEIDOSCOPE DEVELOPERS PVT. LTD. ,

through its Authorized Director





T.I.

SHRI SARANG SUDHAKAR KALE

'THE PURCHASER'





T.I.

LUCIFER ENGINEERS PVT. LTD.,

through its Authorized Director

SHRI SARANG SUDHAKAR KALE

"THE CONSENTING PARTY"

WITNESSES :

1.

Sign.

Name Subodh Apte

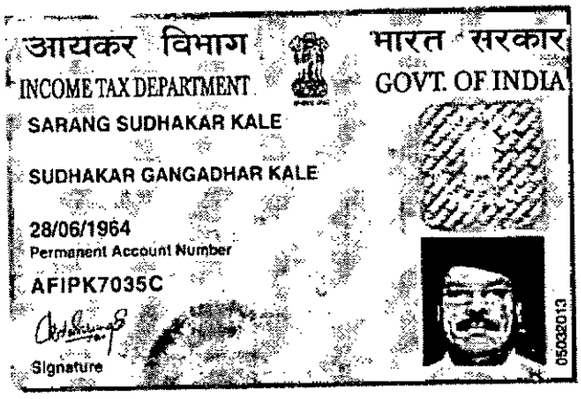
Address Kothrud Nagar, Pune-52

2.

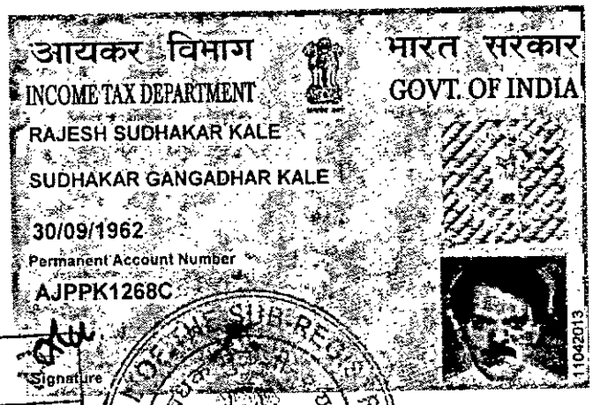
Sign.

Name GAURI MORO

Address KOTHRUD, PUNE-38.




आयकर विभाग
INCOME TAX DEPARTMENT
भारत सरकार
GOVT. OF INDIA
SARANG SUDHAKAR KALE
SUDHAKAR GANGADHAR KALE
28/06/1964
Permanent Account Number
AFIPK7035C
Signature
05032013




आयकर विभाग
INCOME TAX DEPARTMENT
भारत सरकार
GOVT. OF INDIA
RAJESH SUDHAKAR KALE
SUDHAKAR GANGADHAR KALE
30/09/1962
Permanent Account Number
AJPPK1268C
Signature
11042013

म ल स - २
९२३९ | २९ | ९४
२०१६



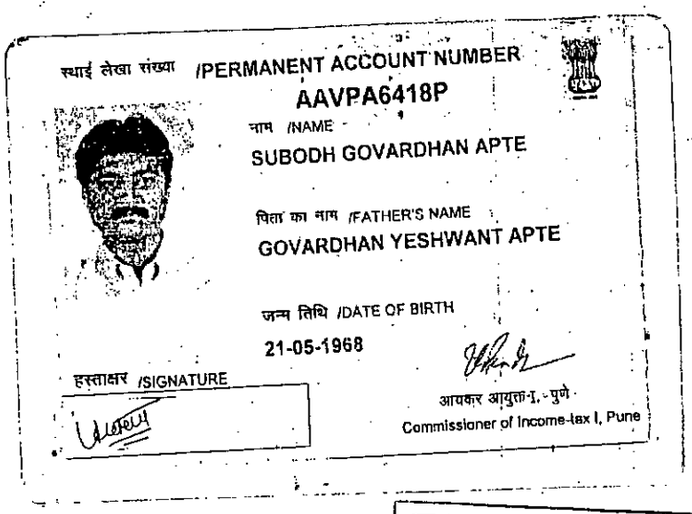
आयकर विभाग
INCOME TAX DEPARTMENT
भारत सरकार
GOVT. OF INDIA
LUCIFER ENGINEERING PRIVATE LIMITED
13/04/2004
Permanent Account Number
AAACL9805B
26012012



आयकर विभाग
INCOME TAX DEPARTMENT
भारत सरकार
GOVT. OF INDIA
KALEIDOSCOPE DEVELOPERS PRIVATE LIMITED
22/06/2010
Permanent Account Number
AAECK0069L
12072010

म ल सं - २		
92369	22	१४५
२०१६		





स्थाई लेखा संख्या /PERMANENT ACCOUNT NUMBER

AAVPA6418P

नाम /NAME

SUBODH GOVARDHAN APTE

पिता का नाम /FATHER'S NAME

GOVARDHAN YESHWANT APTE

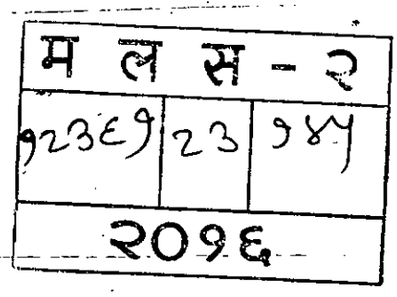
जन्म तिथि /DATE OF BIRTH

21-05-1968

हस्ताक्षर /SIGNATURE

आयकर आयुक्त-१, पुणे


Commissioner of Income-tax I, Pune



म ल स - २

१२३६१	२३	१४५

२०१६



THE SEAL OF THE SUB-REGISTRAR OF

दुय्यम निबंधक मुळशी-२ यांची मुद्रा

सत्यमेव जयते

मुळशी-२

MULSHI - 2



आयकर विभाग

INCOME TAX DEPARTMENT

भारत सरकार

GOVT. OF INDIA

GAURI MANEESH MORO

ULHAS PRALHAD NARGUND


19/06/1979

Permanent Account Number

ADJPN6133D

Signature

म ल स - २		
१२३९१	२४	१४५
२०१६		



म ल स - २
१२३६१ | २५ | १४५
२०१६

THE SEAL OF THE SUB-REGISTRAR OF मुळशी-२ यांची मुद्रा सत्यमेव जयते मुळशी-२ MULSHI-2

Do No. Desk-VI 1582, dt. 4-7-86 From D. G. P. and S. Mumbai] गाव नमुना सात (अधिकार अभिलेख पत्रक) R. V. 24 m.

[महाराष्ट्र जमीन महसूल अधिकार अभिलेख आणि नोंदवह्या (तयार करणे व सुस्थितीत ठेवणे) नियम, १९७१ यातील नियम ३, ५, ६ आणि ७]

गाव **भुगाव** तालुका **मुळशी**

भूमापन क्रमांक	भूमापन क्रमांकाचा उपविभाग	भूधारणा पद्धती
१४१	2	भोगवटदार वर्ग एक
शेताचे स्थानिक नाव	गोठण	

लागवडीयोग्य क्षेत्र	हेक्टर	आर
.....	0	0e·४
.....		
.....		
एकूण	0	0e·४
पोटखराब (लागवडीयोग्य नसलेले)-		
वर्ग (अ) ..		
वर्ग (ब) ..		
एकूण ..	0	0e·४
	रुपये	पैसे
आकारणी ..		
जुडी किंवा विशेष आकारणी ..	0	५e

भोगवटादाराचे नाव

सोपाना नामदेव शेडगे (३३५६)
नंदु केशव शेडगे (७०५१)
पु. कु. मॅ. (७०३५) (६३६४)
(४६६) (१३६०) (१४५१) (१६४८)
पंढरीनाथ शिवराम शेडगे ६६६
पार्वती श्रीपती शेडगे [६६५] (७५३२)
किसन, भाऊ व चंद्रकांत पंढू शेडगे ६६५
(१४४८) (१६३६)
तुकाराम राणू शेडगे ६६८
(३५३) (१७३६) (१६६७)

खाते क्रमांक

कुळाचे नाव खंड / रु. पै.

इतर अधिकार बबुबाई गेनबा चोंधे (३३५६)
तुकडा
(३६३) (१०३४) (१४५०) (१७६८) (१६६७) (४३६३)
सिताबाई एकनाथ शरकुडे
मधुबाई घोंडीबा चोंधे
(१६४६) (३६६७) (६३५४२) (६५८
(६५५) (६५८६) (६६४८) (६७३२)
खंड मध्यपती सुर्वे (६८१६)
सीमा आणि भूमापन चिन्हे
पोपटराव घोडीबा आंग्रे
मारुती घोंडीबा आंग्रे (६५८४)

पुढील पानावर पुरवणी पहा

गाव नमुना बारा (पिकांची नोंदवही)

[महाराष्ट्र जमीन महसूल अधिकार अभिलेख आणि नोंदवह्या (तयार करणे व सुस्थितीत ठेवणे) नियम, १९७१ यातील नियम २९]

वर्ष	हंगाम	पिकाखालील क्षेत्रांचा तपशील: मिश्र पिकाखालील क्षेत्र: मिश्रणाचा संकेत क्रमांक	मिश्र: जल सिंचित	मिश्र: अजल सिंचित	घटक पिके व प्रत्येकाखालील क्षेत्र: पिकाचे नाव	घटक: जल सिंचित	घटक: अजल सिंचित	निर्भेळ पिकाखालील क्षेत्र: पिकाचे नाव	निर्भेळ: जल सिंचित	निर्भेळ: अजल सिंचित	लागवडीसाठी उपलब्ध नसलेली जमीन: स्वरूप	उपलब्ध नसलेली: क्षेत्र	जल सिंचनाचे साधन	जमीन करणाराचे नाव	क्रमांक
१	२	३	४	५	६	७	८	९	१०	११	१२	१३	१४	१५	१६
			हे. आ.	हे. आ.		हे. आ.	हे. आ.		हे. आ.	हे. आ.		हे. आ.			
२०१० / २०११								गोठा पड ०.०e.४						खु.	आंबा १
२०११ / २०१२								गोठा घर ०.०e.४						खु.	—11—
२०१२ / २०१३								गोठा पड ०.०e.४						खु.	—11—
२०१३ / २०१४								गोठा पड ०.०e.४						खु.	—11—

पुढील पानावर पुरवणी पहा

म ल स - २

१३६१ | २६ | १४५

२०१६

THE SEAL OF THE SUB-REGISTRAR OF मुळशी-२ सत्यमेव जयते

LDC 10, Desk VI, 1382, dt. 4-7-85 From D. G. P. and S. Mumbai

गाव नमुना सात (अधिकार अभिलेख पत्रक)

R. V. 24 m.

[महाराष्ट्र जमीन महसूल अधिकार अभिलेख आणि नोंदवह्या (तयार करणे व सुस्थितीत ठेवणे) नियम, १९७१ यातील नियम ३, ५, ६ आणि ७]

गाव **भुगाव** तालुका **मुळशी**

भूमापन क्रमांक	भूमापन क्रमांकाचा उपविभाग	भूधारणा पद्धती
१४१	२-ची पुरवणी	नं. १
शेताचे स्थानिक नाव		

लागवडीयोग्य क्षेत्र	हेक्टर	आर
.....		
.....		
.....		
एकूण		
पोटखराब (लागवडीयोग्य नसलेले)-		
वर्ग (अ) ..		
वर्ग (ब) ..		
एकूण ..		
	रुपये	पैसे
आकारणी ..		
जुडी किंवा विशेष आकारणी ..		

भोगवटादाराचे नाव

रामभाऊ सोपाना शेडगे
दामु सोपाना शेडगे
इंदुमती बबन शेडगे
मैनाबाई दिलीप सणस
संजाबाई सोपान मारणे
सावित्रा बबन शेडगे
शिवाजी बबन शेडगे
(३१३२)
भाऊ व बबन गेनू शेडगे
६८४ ६८४
सुरेश शंकर शेडगे
६८४
गोदाबाई गणपत ससार
गंऊबाई गणपत ससार
(१९१६) (१७६८) (१८४८) (१८४९) (१९२९)

खाते क्रमांक

कुळाचे नाव खंड रु. पै.

इतर अधिकार

मीनाबाई मारुती हरपळे
(६८४)

सीमा आणि भूमापन चिन्हे

पुढील पान १९२ पुरवणी पहा

गाव नमुना बारा (पिकांची नोंदवही)

[महाराष्ट्र जमीन महसूल अधिकार अभिलेख आणि नोंदवह्या (तयार करणे व सुस्थितीत ठेवणे) नियम, १९७१ यातील नियम २९]

वर्ष	हंगाम	पिकाखालील क्षेत्रांचा तपशील									लागवडीसाठी उपलब्ध नसलेली जमीन		जल सिंचनाचे साधन	जमीन करणाराचे नाव	शेरा
		मिश्र पिकाखालील क्षेत्र						निर्भेळ पिकाखालील क्षेत्र							
		मिश्रणाचा संकेत क्रमांक	जल सिंचित	अजल सिंचित	घटक पिके व प्रत्येकाखालील क्षेत्र: पिकाचे नाव	जल सिंचित	अजल सिंचित	पिकाचे नाव	जल सिंचित	अजल सिंचित	स्वरूप	क्षेत्र			
१	२	३	४	५	६	७	८	९	१०	११	१२	१३	१४	१५	१६
			हे. आ.	हे. आ.		हे. आ.	हे. आ.		हे. आ.	हे. आ.		हे. आ.			

पुढील पानावर पुरवणी पहा

म ल स - २		
१२३६१	२७	१४५
२०१६		

THE SEAL OF THE SUB-REGISTRAR OF मुळशी-२ यांची मुद्रा मुळशी-२ MULSHI - 2

Do No. Desk-VI-1562, dt. 4-7-86 From D. G. P. and S. Mumbai] गाव नमुना सात (अधिकार अभिलेख पत्रक) — R. V. 24 m.

[महाराष्ट्र जमीन महसूल अधिकार अभिलेख आणि नोंदवह्या (तयार करणे व सुस्थितीत ठेवणे) नियम, १९७१ यातील नियम ३, ५, ६ आणि ७]

गाव **मुगाव** तालुका **मुळशी**

भूमापन क्रमांक	भूमापन क्रमांकाचा उपविभाग	भूधारणा पद्धती
१४१	२ ची पुरवणी	नं. २
शेताचे स्थानिक नाव		

लागवडीयोग्य क्षेत्र	हेक्टर	आर
.....		
.....		
.....		
एकूण		
पोट (लागवडीयोग्य नसलेले)-		
वर्ग (अ) ..		
वर्ग (ब) ..		
एकूण ..		
आकारणी ..	रुपये	पैसे
जुडी किंवा विशेष आकारणी ..		

भोगवटादाराचे नाव

नारायण नामदेव शेडगे
हरिभाऊ नामदेव शेडगे
मनोहर नामदेव शेडगे
६८४
(१३३५) (१८७९) (१९४९)
गोनभाऊ पिराजी शेडगे
सिताराम तुकाराम शेडगे
पांडुरंग तुकाराम शेडगे
विठ्ठल तुकाराम शेडगे
ज्ञानोबा तुकाराम शेडगे
शारुन महादेव चोंधे
फुलाबाई खंडू चोंधे
गिताबाई तुकाराम शेडगे
६८८
(३२५९)

खाते क्रमांक

कुळाचे नाव खंड

रु. पै.

इतर अधिकार

सीमा आणि भूमापन चिन्हे

पुढील पानावर पुरवणी पहा

गाव नमुना बारा (पिकांची नोंदवही)

[महाराष्ट्र जमीन महसूल अधिकार अभिलेख आणि नोंदवह्या (तयार करणे व सुस्थितीत ठेवणे) नियम, १९७१ यातील नियम २९]

वर्ष	हंगाम	पिकाखालील क्षेत्रांचा तपशील									लागवडीसाठी उपलब्ध नसलेली जमीन		जल सिंचनाचे साधन	जमीन कसणाऱ्याचे नाव	शेरा
		मिश्र पिकाखालील क्षेत्र						निर्भेळ पिकाखालील क्षेत्र							
					घटक पिके व प्रत्येका-खालील क्षेत्र										
		भिन्नपाचा संकेत क्रमांक	जल सिंचित	अजल सिंचित	पिकाचे नाव	जल सिंचित	अजल सिंचित	पिकाचे नाव	जल सिंचित	अजल सिंचित	स्वरूप	क्षेत्र			
१	२	३	४	५	६	७	८	९	१०	११	१२	१३	१४	१५	१६
			हे. आ.	हे. आ.		हे. आ.	हे. आ.		हे. आ.	हे. आ.		हे. आ.			

पुढील पानावर पुरवणी पहा

न ल स - २

१२३९ २९/१४१

२०१६

THE SEAL OF THE SUB-REGISTRAR OF मुळशी-२

(Do No. Desk-VI/ 1582, dt. 4-7-86 From D. G. P. and S. Mumbai) गाव नमुना सात (अधिकार अभिलेख पत्रक) R. V. 24 m.

[महाराष्ट्र जमीन महसूल अधिकार अभिलेख आणि नोंदवह्या (तयार करणे व सुस्थितीत ठेवणे) नियम, १९७१ यातील नियम ३, ५, ६ आणि ७]

गाव **भुगाव** तालुका **मुळशी**

भूमापन क्रमांक	भूमापन क्रमांकाचा उपविभाग	भूधारणा पद्धती
१४१	2 ची पुरवणी	नं. 3
शेताचे स्थानिक नाव		

लागवडीयोग्य क्षेत्र	हेक्टर	आर
.....		
.....		
.....		
एकूण		
पोटखराब (लागवडीयोग्य नसलेले)-		
वर्ग (अ) ..		
वर्ग (ब) ..		
एकूण ..		
आकारणी ..	रुपये	पैसे
जुडी किंवा विशेष आकारणी ..		

भोगवटादाराचे नाव

पारुबाई दशरथ शेडगे
६३६४
३९९७ ४१९५

चंद्रकांत नारायण साळुंके
६१६४
४४८८ ५४१९ ५४१७ ५४५८
५५९३ ५९२३ रु

सारंग सुधाकर काळे
००हे ०५ आर + ०१ ०=००१९३
६१५४ ६३०१ ६३८९ ६३९६ आर ६६६८
६३९७

सारंग सुधाकर काळे
राजेश सुधाकर काळे
०.००.६३ आर
६६६०

खाते क्रमांक

कुळाचे नाव. खंड
रु. पै.

इतर अधिकार

सीमा आणि भूमापन चिन्हे

गाव नमुना बारा (पिकांची नोंदवही)

[महाराष्ट्र जमीन महसूल अधिकार अभिलेख आणि नोंदवह्या (तयार करणे व सुस्थितीत ठेवणे) नियम, १९७१ यातील नियम २९]

२) सोना बारु चाकु निंबाळे
३) गंगु बारु निंबाळे

वर्ष	हंगाम	पिकाखालील क्षेत्रांचा तपशील: मिश्र पिकाखालील क्षेत्र						निव्वळ पिकाखालील क्षेत्र				जमीन महसूल	जल सिंचनाचे साधन	जमीन करणाऱ्याचे नाव	शेरा
		मिश्रणाचा संकेत क्रमांक	जल सिंचित	अजल सिंचित	घटक पिके व प्रत्येकाखालील क्षेत्र: पिकाचे नाव	जल सिंचित	अजल सिंचित	पिकाचे नाव	जल सिंचित	अजल सिंचित	एकूण				
१	२	३	४	५	६	७	८	९	१०	११	१२	१३	१४	१५	१६
			हे. आ.	हे. आ.		हे. आ.	हे. आ.		हे. आ.	हे. आ.		हे. आ.			
								१) पुतळाबाई २) सुनिल ३) अनिल नंबु शेडगे ४) जयश्री प्रविण धनेश मनोहर शेडगे अ. पु ६६ चे म ५१ ६ ४				(६६५)		१) हिरामण पर्वती शेडगे २) वसंत पर्वती शेडगे ३) दत्तात्रय पर्वती शेडगे ४) लिलाबाई चतुरभान घरुडे ५) रंजना आबाजी वरघडे ६६५ (५३२)	पुरवणी १+३ = ४ असे तलाठी सजा मारुंजी: २३ JAN 2014 कार्यालय तलाठी मौजे भुगांव, ता. मुळशी, जि. पुणे (श्रीमती. शिंदे एस. एस.)
								६) अनंता बाबु निंबाळे ७) निर्मला निवृत्ती पडवे ८) लिला रामराव गेरिं ९) सुरेखा पोपट कंद १०) राम बाबु निंबाळे				(६६५)			

म ल स - २

१२३६१ | २९ | १४५

२०१६

THE SEAL OF THE SUB-REGISTRAR OF मुळशी-२ दुय्यम निबंधक

Do No. Desk-VI 1582 dt. 2-7-96 From D. G. P. and S. Mumbai

गाव नमुना सात (अधिकार अभिलेख पत्रक)

R. V. 24 m.

[महाराष्ट्र जमीन महसूल अधिकार अभिलेख आणि नोंदवह्या (तयार करणे व सुस्थितीत ठेवणे) नियम, १९७१ यातील नियम ३, ५, ६ आणि ७]

गाव **भुगाव** तालुका **मुळशी**

भूमापन क्रमांक	भूमापन क्रमांकाचा उपविभाग	भूधारणा पद्धती
१४१	५	भोगवटादार वर्ग १

शेताचे स्थानिक नाव: आगळ्याची विहीर

लागवडीयोग्य क्षेत्र	हेक्टर	आर
.....	०	०२.५
.....		
.....		
एकूण	०	०२.५
पोटखराब (लागवडीयोग्य नसलेले)-	०	०१.३
वर्ग (अ) ..		
वर्ग (ब) ..		
एकूण ..	०	०३.८
	रुपये	पैसे
आकारणी ..		
जुडी किंवा विशेष आकारणी ..	०	१२

भोगवटादाराचे नाव

सोपान खंडू शेडगे
६६८
(१३९०) (१९३४)

पंढरीनाथ शिवराम शेडगे
६६९

~~पर्वती श्रीपती शेडगे~~
[६६५]

किसन, भाऊ व चंद्रकांत पद्मू शेडगे
६६५
(१९३९)

रेऊ को. सोपाना शेडगे
६१६४
(३५३) (१९६७)

तुकाराम शंभू शेडगे
६६८
(१७३४) (१७३६)

खाते क्रमांक

कुळाचे नाव: खंड रु. पै.

इतर अधिकार

भागूबाई महिपती सुर्वे
अनुसया तुकाराम पठारे
जनाबाई धोंडीबा आंग्रे
(१७६९) (४३६३)

[सिताबाई गुरुनाथ शरकुडे
मधुबाई धोंडीबा चोंधे
(१९४९) (३९६७)

तुकडा (३६३) (१७९९) (१५०७) (१९६७) (६१५६)

सीमा आणि भूमापन चिन्हे

१) ताराबाई बबन सुतार
२) बबाबाई बबन झाल्के
पुढील पानावर पुरवणी पहा

गाव नमुना बारा (पिकांची नोंदवही)

[महाराष्ट्र जमीन महसूल अधिकार अभिलेख आणि नोंदवह्या (तयार करणे व सुस्थितीत ठेवणे) नियम, १९७१ यातील नियम २९]

वर्ष	हंगाम	पिकाखालील क्षेत्रांचा तपशील: मिश्र पिकाखालील क्षेत्र: पिकाचा संकेत क्रमांक	मिश्र: जल सिंचित	मिश्र: अजल सिंचित	मिश्र: घटक पिके व प्रत्येकाखालील क्षेत्र: पिकाचे नाव	मिश्र: जल सिंचित	मिश्र: अजल सिंचित	निर्भेळ पिकाखालील क्षेत्र: पिकाचे नाव	निर्भेळ: जल सिंचित	निर्भेळ: अजल सिंचित	लागवडीसाठी उपलब्ध नसलेली जमीन: खरब	लागवडीसाठी उपलब्ध नसलेली जमीन: इतर क्षेत्र	जल सिंचनाचे साधन	जमीन कारणाराचे नाव	शेरा
१	२	३	४	५	६	७	८	९	१०	११	१२	१३	१४	१५	१६
			हे. आ.	हे. आ.		हे. आ.	हे. आ.		हे. आ.	हे. आ.		हे. आ.			
२०१०/२०११								वि. पड ०.०२.५						खु.	आंबा १
२०११/२०१२								वि. पड ०.०२.५						खु.	—11—
२०१२/२०१३								वि. पड ०.०२.५						खु.	—11—
२०१३/२०१४								वि. पड ०.०२.५						खु.	—11—

पुढील पानावर पुरवणी पहा

ग न मु - २

१२३९/३० १४५

THE SEAL OF THE SUB-REGISTRAR OF MULSHI R.V. 24 m.

Do No. Desk-VI-1582 dt. 4-7-86 From D. O. P. and S. Mumbai] गाव नमुना सात (अधिकार अभिलेख पत्रक)

[महाराष्ट्र जमीन महसूल अधिकार अभिलेख आणि नोंदवह्या (तयार करणे व सुस्थितीत ठेवणे) नियम, १९७१ यातील नियम ३, ५, ६ आणि ७]

गाव **भुगाव** तालुका **मुळशी**

भूमापन क्रमांक	भूमापन क्रमांकाचा उपविभाग	भूधारणा पद्धती
१४१	५ ची पुरवणी	नं. १
शेताचे स्थानिक नाव		

लागवडीयोग्य क्षेत्र	हेक्टर	आर
.....		
.....		
.....		
एकूण		
पोटखराब (लागवडीयोग्य नसलेले)-		
वर्ग (अ) ..		
वर्ग (ब) ..		
एकूण ..		
	रुपये	पैसे
आकारणी ..		
जुडी किंवा विशेष आकारणी ..		

भोगवटादाराचे नाव
बबन गेनू शेडगे
६८४
(१९२९)
दत्तात्रय नारायण शेडगे
६८४
सुरेश शंकर शेडगे अ.पा.क.
आई वत्सलाबाई
६८४
(१९६९) (१९२९) (१९४८) (१९४९)
१) दत्तू व २) उत्तम बाबूराव शेडगे
(३१३०)
नारायण नामदेव शेडगे
हरिभाऊ नामदेव शेडगे
मनोहर नामदेव शेडगे
(१९४९)

खाते क्रमांक
कुळाचे नाव खंड
रु. पै.

इतर अधिकार
३) पार्वतीबाई सोपान कड
(२०८०)
बबुबाई गेनबा चोंधे
(३३५९)
(४७८७) (५०९४) (६५६७ रद्द)

सीमा आणि भूमापन चिन्हे
पुढील पानावर पुरवणी पहा

गाव नमुना बारा (पिकांची नोंदवही)

[महाराष्ट्र जमीन महसूल अधिकार अभिलेख आणि नोंदवह्या (तयार करणे व सुस्थितीत ठेवणे) नियम, १९७१ यातील नियम २९]

वर्ष	हंगाम	पिकाखालील क्षेत्रांचा तपशील									लागवडीसाठी उपलब्ध नसलेली जमीन		जल सिंचनाचे साधन	जमीन कसणाऱ्याचे नाव	शेरा
		मिश्र पिकाखालील क्षेत्र						निर्भेळ पिकाखालील क्षेत्र							
		मिश्रणाचा संकेत क्रमांक	जल सिंचित	अजल सिंचित	घटक पिके व प्रत्येका-खालील क्षेत्र						प्रकार	क्षेत्र			
					पिकाचे नाव	जल सिंचित	अजल सिंचित	पिकाचे नाव	जल सिंचित	अजल सिंचित					
१	२	३	४	५	६	७	८	९	१०	११	१२	१३	१४	१५	१६
			हे. आ.	हे. आ.		हे. आ.	हे. आ.		हे. आ.	हे. आ.		हे. आ.			

पुढील पानावर पुरवणी पहा

म ल स - २

१२३९ | ३९ | १४५

२०१६

THE SEAL OF THE SUB-REGISTRAR OF मुख्य निबंधक मुळशी-२ यांची मुद्रा सत्यमेव जयते मुळशी-२ MULSHI-2

Govt. Ins. Press, Dhl. & 7-10 Prem. D. G. P. and S. Mumbai

गाव नमुना सात (अधिकार अभिलेख पत्रक)

R. V. 24 m.

[महाराष्ट्र जमीन महसूल अधिकार अभिलेख आणि नोंदवह्या (तयार करणे व सुस्थितीत ठेवणे) नियम, १९७१ यातील नियम ३, ५, ६ आणि ७]

गाव **भुगाव** तालुका **मुळशी**

भूमापन क्रमांक	भूमापन क्रमांकाचा उपविभाग	भूधारणा पद्धती
१४१	५ ची पुरवणी	नं. २
शेताचे स्थानिक नाव		

लागवडीयोग्य क्षेत्र	हेक्टर	आर
.....		
.....		
.....		
एकूण		
पोटखराब (लागवडीयोग्य नसलेले)-		
वर्ग (अ) ..		
वर्ग (ब) ..		
एकूण ..		
	रुपये	पैसे
आकारणी ..		
जुडी किंवा विशेष आकारणी ..		

भोगवटादाराचे नाव

बाबू भाऊ शेडगे
दिलीप भाऊ शेडगे
लक्ष्मीबाई राम मते
जबुबाई मधुकर भेगडे
कासाबाई पुकनाथ चोंधे
बाळाबाई आप्पा सोनार
मंगल दत्तु रिंडे
गुलाब जयसिंग कुडले
८८४
(४५२४)
गणपत शामा शेडगे
श्रीपती शामा शेडगे
किसन शामा शेडगे
६६८

खाते क्रमांक

कुळाचे नाव खंड

रु. पै.

इतर अधिकार

सीमा आणि भूमापन चिन्हे

पुढील पानावर पुरवणी पहा

गाव नमुना बारा (पिकांची नोंदवही)

[महाराष्ट्र जमीन महसूल अधिकार अभिलेख आणि नोंदवह्या (तयार करणे व सुस्थितीत ठेवणे) नियम, १९७१ यातील नियम २९]


वर्ष	हंगाम	पिकाखालील क्षेत्रांचा तपशील									लागवडीसाठी उपलब्ध नसलेली जमीन		जल सिंचनाचे साधन	जमीन करणाऱ्याचे नाव	शेरा
		मिश्र पिकाखालील क्षेत्र						निर्भेळ पिकाखालील क्षेत्र							
					घटक पिके व प्रत्येकाखालील क्षेत्र										
		पिकाखालील क्षेत्राचा संकेत क्रमांक	जल सिंचित	अजल सिंचित	पिकाचे नाव	जल सिंचित	अजल सिंचित	पिकाचे नाव	जल सिंचित	अजल सिंचित	स्वरूप	क्षेत्र			
१	२	३	४	५	६	७	८	९	१०	११	१२	१३	१४	१५	१६
			हे. आ.	हे. आ.		हे. आ.	हे. आ.		हे. आ.	हे. आ.		हे. आ.			

पुढील पानावर पुरवणी पहा

म ल स - २

१२३६/३२/१४

२०१६



गाव नमुना सात (अधिकार अभिलेख पत्रक) R. V. 24 m.

[महाराष्ट्र जमीन महसूल अधिकार अभिलेख आणि नोंदवह्या (तयार करणे व सुस्थितीत ठेवणे) नियम, १९७१ यातील नियम ३, ५, ६ आणि ७]

गाव **भुगाव** तालुका **मुळशी**

भूमापन क्रमांक	भूमापन क्रमांकाचा उपविभाग	भूधारणा पद्धती
१४१	५ ची पुरवणी	नं. ३
शेताचे स्थानिक नाव		

लागवडीयोग्य क्षेत्र	हेक्टर	आर
.....		
.....		
.....		
एकूण		
पोटखराब (लागवडीयोग्य नसलेले)-		
वर्ग (अ) ..		
वर्ग (ब) ..		
एकूण ..		
	रुपये	पैसे
आकारणी ..		
जुडी किंवा विशेष आकारणी ..		

भोगवटादाराचे नाव

पिरा तुकाराम शेडगे
६६४
(१३३५) (१८७९)
दशरथ नामदेव शेडगे
सोपाना नामदेव शेडगे
६२६२
(३३५६)
नंदू केशव शेडगे (७०५१)
(पु.कु.मै.) (७०३५)
(६२६२)
१) दशरथ शंकर सुर्वे
२) दत्तु शंकर सुर्वे
६२६८
(४९८) (८३३) (२०८०)
पुष्पा मारुती बोरकर
(१७६२) (३१३०) (३५२९) (३९६७) (६३०१)

खाते क्रमांक

कुळाचे नाव खंड

रु. पै.

इतर अधिकार

सीमा आणि भूमापन चिन्हे

पुढील पानावर पुरवणी पहा

गाव नमुना बारा (पिकांची नोंदवही)

[महाराष्ट्र जमीन महसूल अधिकार अभिलेख आणि नोंदवह्या (तयार करणे व सुस्थितीत ठेवणे) नियम, १९७१ यातील नियम २९]

वर्ष	हंगाम	पिकाखालील क्षेत्रांचा तपशील									लागवडीसाठी उपलब्ध नसलेली जमीन		जल सिंचनाचे साधन	जमीन कारणाचे नाव	शेरा
		मिश्र पिकाखालील क्षेत्र						निर्भेळ पिकाखालील क्षेत्र							
		मिश्रणाचा संकेत क्रमांक	जल सिंचित	अजल सिंचित	घटक पिके व प्रत्येकाखालील क्षेत्र			पिकाचे नाव	जल सिंचित	अजल सिंचित	स्वरूप	क्षेत्र			
					पिकाचे नाव	जल सिंचित	अजल सिंचित								
१	२	३	४	५	६	७	८	९	१०	११	१२	१३	१४	१५	१६
			हे. आ.	हे. आ.		हे. आ.	हे. आ.		हे. आ.	हे. आ.		हे. आ.			

पुढील पानावर पुरवणी पहा

म ल स - २

१२३६१	३३	१४५
२०१६		

THE SEAL OF THE SUB-REGISTRAR OF मुद्रांक निबंधक मुळशी-२ यांची मुद्रा सत्यमेव जयते मुळशी-२ MULSHI-2

[illegible] गाव नमुना सात (अधिकार अभिलेख पत्रक) -- R. V. 24 m.

[महाराष्ट्र जमीन महसूल अधिकार अभिलेख आणि नोंदवह्या (तयार करणे व सुस्थितीत ठेवणे) नियम, १९७१ यातील नियम ३, ५, ६ आणि ७]

गाव **भुगाव** तालुका **मुळशी**

भूमापन क्रमांक	भूमापन क्रमांकाचा उपविभाग	भूधारणा पद्धती
१४१	५ ची पुरवणी	नं. ४
शेताचे स्थानिक नाव		

लागवडीयोग्य क्षेत्र	हेक्टर	आर
.....		
.....		
.....		
एकूण		
पोटखराब (लागवडीयोग्य नसलेले)-		
वर्ग (अ) ..		
वर्ग (ब) ..		
एकूण ..		
आकारणी ..	रुपये	पैसे
जुडी किंवा विशेष आकारणी ..		

भोगवटादाराचे नाव

५४१६ ५४१७ ५५६३ ५६२३ २६

साईश सुधाकर काळे

राजेश सुधाकर काळे

०.००.३

६६६०

सारंग सुधाकर काळे

क्षेत्र ०-००१०६ आर

६६६६ [illegible] सोनाबाई बाबु मिसाळ

[illegible] मधुकर ईश्वर शेळके

७०३५

श्रीपुलाबाई २ सुनिल ३ अनिल

नंदु शेडगे ५ जयश्री ६ विशाल

७ विनय मनोहर शेडगे ८ ५४६

म.प.क्र ४ ७५१ ६२६८

१ अनंता बाबु मिसाळ २ निर्मिला

निवृत्ती पाडळे ३ लिला रामराव गोडे

४ सुरेखा श्रीधर केदारी ५ राम बाबु मिसाळ

खाते क्रमांक

कुळाचे नाव खंड

रु. पै.

इतर अधिकार

सीमा आणि भूमापन चिन्हे

गाव नमुना बारा (पिकांची नोंदवही) ७२५१

[महाराष्ट्र जमीन महसूल अधिकार अभिलेख आणि नोंदवह्या (तयार करणे व सुस्थितीत ठेवणे) नियम, १९७१ यातील नियम २९]

वर्ष १	हंगाम २	पिकाखालील क्षेत्रांचा तपशील: मिश्र पिकाखालील क्षेत्र: मिश्रणाचा संकेत क्रमांक ३	जल सिंचित ४	अजल सिंचित ५	घटक पिके व प्रत्येकाखालील क्षेत्र: पिकाचे नाव ६	जल सिंचित ७	अजल सिंचित ८	निर्भेळ पिकाखालील क्षेत्र: पिकाचे नाव ९	जल सिंचित १०	अजल सिंचित ११	लागवडीसाठी उपलब्ध नसलेली जमीन: स्वरूप १२	क्षेत्र १३	जल सिंचनाचे साधन १४	जमीन करणाराचे नाव १५	शेरा १६
			हे. आ.	हे. आ.		हे. आ.	हे. आ.		हे. आ.	हे. आ.		हे. आ.			
														१ विठाबाई पुंडलीक शेडगे २ वसंत पुंडलीक शेडगे ३ हनुमंत पुंडलीक शेडगे ४ लिलाबाई चंद्रभान थरकुडे ५ रेखा आबाजी वधरे ६५ ७५३२	पुरवणी १+४ = ५ असे [illegible] तलाठी [illegible] मुळशी, [illegible] जि. पुणे ([illegible])

म ल स - २

१२३९/३५ १४५

२०१६

THE SEAL OF THE SUB-REGISTRAR OF दुय्यम निबंधक मुळशी-२ यांची मोहर सत्यमेव जयते मुळशी-२

Do No. Desk-VI. 1582, dt. 4-7-86 From D. O. P. and S. Mumbai] गाव नमुना सात (अधिकार अभिलेख पत्रक) R. V. 24 m.

[महाराष्ट्र जमीन महसूल अधिकार अभिलेख आणि नोंदवहा (तयार करणे व सुस्थितीत ठेवणे) नियम, १९७१ यातील नियम ३, ५, ६ आणि ७]

गाव **भुगाव** तालुका **मुळशी**

भूमापन क्रमांक	भूमापन क्रमांकाचा उपविभाग	भूधारणा पद्धती
१४३		भोगवटादार वर्ग २

शेताचे स्थानिक नाव पिराची आडव

लागवडीयोग्य क्षेत्र	हेक्टर	आर
.....	५	२७
.....		
.....		
एकूण	५	२७
पोटखराब (लागवडीयोग्य नसलेले)-		
वर्ग (अ) ..	०	२०
वर्ग (ब) ..		
एकूण ..	५	५६
	रुपये	पैसे
आकारणी ..		
जुडी किंवा विशेष आकारणी ..	६	५०

भोगवटादाराचे नाव (४४८) ३५३ ३७२ ८३३ ८४३ १३८० १४४८ १४५१ १७६० १८४८ १८४८ १८६७ ३३५६ ५१५५

रामभाऊ सोपाना शेडगे
दामु सोपाना शेडगे
इंदुमती बबन शेडगे
मैनाबाई दिलीप सणस
संजाबाई सोपान मारणे
सावित्रा बबन शेडगे
शिवाजी बबन शेडगे
अ.पा.क. आई इंदुमती (३९३२)
१३३५ १६१६ १६८३ १८४८ १८४८ १८७५ १७६८

खाते क्रमांक
कुळाचे नाव खंड
रु. पै.

इतर अधिकार
३६३ १४५० १७६८ १८४८ १८८६ १८४८ १८६७ ४३६३
बबुबाई गेनबा चोंधे
३३५६ ३८६७ ६२०२
इकशार २.हे.५०००/-
२०/२/८१
३३५३ ६२१३ ६३५४ २६ ६७३२ ६५८४ ६५८५ ६५८६ ६६४८
सीमा आणि भूमापन चिन्हे
खडे मोहिती सुर्वे पोपटराव घोडीबा आंबे (६५०)
पुढील पानावर पुरवणी पहा

गाव नमुना बारा (पिकांची नोंदवही)

[महाराष्ट्र जमीन महसूल अधिकार अभिलेख आणि नोंदवहा (तयार करणे व सुस्थितीत ठेवणे) नियम, १९७१ यातील नियम २९]

सुरेश रामु शेडगे दि.पा.क. वत्सलाबाई ८६

वर्ष	हंगाम	पिकाखालील क्षेत्रांचा तपशील: मिश्र पिकाखालील क्षेत्र: मिश्रणाचा संकेत क्रमांक	जल सिंचित	अजल सिंचित	घटक पिके व प्रत्येकाखालील क्षेत्र: पिकाचे नाव	जल सिंचित	अजल सिंचित	निर्भेळ पिकाखालील क्षेत्र: पिकाचे नाव	जल सिंचित	अजल सिंचित	लागवडीसाठी उपलब्ध नसलेली जमीन: स्वरूप	क्षेत्र	जल सिंचनाचे साधन	जमीन करणाराचे नाव	शेरा
१	२	३	४	५	६	७	८	९	१०	११	१२	१३	१४	१५	१६
			हे.आ.	हे.आ.		हे.आ.	हे.आ.		हे.आ.	हे.आ.		हे.आ.			
२०१०/२०११								गा.पड ५.२७						खंडु	आंबे २
२०११/२०१२								गा.पड ५.२७						खंडु	—"—
२०१२/२०१३								गा.पड ५.२७						खंडु	—"—
२०१३/२०१४								गा.पड ५.२७						खंडु	—"—

पुढील पानावर पुरवणी पहा

म ल स - २

९२३९ | ३५ | १४५

२०१६

THE SEAL OF THE SUB-REGISTRAR OF मुळशी-२ MULSHI-2

म. गा. २४ म.
R. V. 24 m.

Do No. Desk-VI-1582, dt. 4-7-86 From D. G. P. and S. Mumbai) गाव नमुना सात (अधिकार अभिलेख पत्रक)

[महाराष्ट्र जमीन महसूल अधिकार अभिलेख आणि नोंदवह्या (तयार करणे व सुस्थितीत ठेवणे) नियम, १९७१ यातील नियम ३, ५, ६ आणि ७]

गाव **भुगाव** तालुका **मुळशी**

भूमापन क्रमांक	भूमापन क्रमांकाचा उपविभाग	भूधारणा पद्धती
१४३	ची पुरवणी	नं. १
शेताचे स्थानिक नाव		

लागवडीयोग्य क्षेत्र	हेक्टर	आर
.....		
.....		
.....		
एकूण		
पोटखराब (लागवडीयोग्य नसलेले)-		
वर्ग (अ) ..		
वर्ग (ब) ..		
एकूण ..		
	रुपये	पैसे
आकारणी ..		
जुडी किंवा विशेष आकारणी ..		

भोगवटादाराचे नाव
अनुसयाबाई बाबुराव मोकाशी
(३९९७) (६२१९)
बाबू भाऊ शेडगे
दिलीप भाऊ शेडगे
लक्ष्मीबाई राम मते
जबुबाई मधुकर भेगडे
कासाबाई पुकनाथ चोंधे
बाळाबाई आप्पा सोनार
मंगल दत्तु रिंडे
गुलाब जयसिंग कुडले
८८४
(४५२४)
(५३९५) (५४१६) (५४५८) (५४९२)
(५५६३) (५९९०) (६१४५) (६२१३)
(६५६१२६)

खाते क्रमांक
कुळाचे नाव खंड
रु. पै.

इतर अधिकार
मारुती धोंडीबा ओंग्रे
मीनाबाई मारुती हरपळे
(६५८४)

सीमा आणि भूमापन चिन्हे

पुढील पानावर पुरवणी पहा

गाव नमुना बारा (पिकांची नोंदवही)

[महाराष्ट्र जमीन महसूल अधिकार अभिलेख आणि नोंदवह्या (तयार करणे व सुस्थितीत ठेवणे) नियम, १९७१ यातील नियम २९]

वर्ष	रंगाम	पिकाखालील क्षेत्रांचा तपशील									लागवडीसाठी उपलब्ध नसलेली जमीन		जल सिंचनाचे साधन	जमीन करणाऱ्याचे नाव	शेरा
		मिश्र पिकाखालील क्षेत्र			घटक पिके व प्रत्येकाखालील क्षेत्र			निर्भेळ पिकाखालील क्षेत्र							
		मिश्रणाचा संकेत क्रमांक	जल सिंचित	अजल सिंचित	पिकाचे नाव	जल सिंचित	अजल सिंचित	पिकाचे नाव	जल सिंचित	अजल सिंचित	हद्दपार	क्षेत्र			
१	२	३	४	५	६	७	८	९	१०	११	१२	१३	१४	१५	१६
			हे. आ.	हे. आ.		हे. आ.	हे. आ.		हे. आ.	हे. आ.		हे. आ.			

पुढील पानावर पुरवणी पहा

प ल स - २

९२३६१३६ $४५

THE SEAL OF THE SUB-REGISTRAR OF ... MULSHI

Do No. Desk-VI/ ... 1582, dt. 4-7-86 From D. G. P. of S. Mumbai]

गाव नमुना सात (अधिकार अभिलेख पत्रक)

[महाराष्ट्र जमीन महसूल अधिकार अभिलेख आणि नोंदवह्या (तयार करणे व सुस्थितीत ठेवणे) नियम, १९७१ यातील नियम ३, ५, ६ आणि ७]

गाव **भुगाव** तालुका **मुळशी**

भूमापन क्रमांक	भूमापन क्रमांकाचा उपविभाग	भूधारणा पद्धती
१४३	ची पुरवणी	नं. २
शेताचे स्थानिक नाव		

लागवडीयोग्य क्षेत्र	हेक्टर	आर
.....		
.....		
.....		
एकूण		
पोटखराब (लागवडीयोग्य नसलेले)-		
वर्ग (अ) ..		
वर्ग (ब) ..		
एकूण ..		
	रुपये	पैसे
आकारणी ..		
जुडी किंवा विशेष आकारणी ...		

भोगवटादाराचे नाव

सारंग सुधाकर काळे

००ह े २३.१६ आर

(६१०७) (६१२६)

२.२०.१६ आर

(६३६६) (६३६७) ००ह े ०७.६३ (६२३३)

(३५१७) (३५५७) (४१६५) (४४८८)

(४६६६) (५०६५) (५१५३) (५१५५)

(५४१६) (५४१७) (५६२३ रद्द)

श्रीधर धोंडीबा घुमाळ

अशोक गजानन यादव

संजय दत्तात्रय काकडे

क्षेत्र १ ह े ३६

(६२५६)

खाते क्रमांक

कुळाचे नाव खंड

रु. पै.

इतर अधिकार

सीमा आणि भूमापन चिन्हे

पुढील पान १९२ पुरवणी पहा

गाव नमुना बारा (पिकांची नोंदवही)

[महाराष्ट्र जमीन महसूल अधिकार अभिलेख आणि नोंदवह्या (तयार करणे व सुस्थितीत ठेवणे) नियम, १९७१ यातील नियम २९]

वर्ष	हंगाम	पिकाखालील क्षेत्रांचा तपशील									लागवडीसाठी उपलब्ध नसलेली जमीन		जल सिंचनाचे साधन	जमीन कारणाराचे नाव	शेरा
		मिश्र पिकाखालील क्षेत्र			घटक पिके व प्रत्येका-खालील क्षेत्र			निर्भेळ पिकाखालील क्षेत्र							
		मिश्रणाचा संकेत क्रमांक	जल सिंचित	अजल सिंचित	पिकाचे नाव	जल सिंचित	अजल सिंचित	पिकाचे नाव	जल सिंचित	अजल सिंचित	खाडक्षर	क्षेत्र			
१	२	३	४	५	६	७	८	९	१०	११	१२	१३	१४	१५	१६
			हे. आ.	हे. आ.		हे. आ.	हे. आ.		हे. आ.	हे. आ.		हे. आ.			

पुढील [illegible] पुरवणी पहा

म ल स - २

१२३६१३५ | १४५

२०१६

THE SEAL OF THE SUB-REGISTRAR OF मुळशी क्रमांक २ यांची मुद्रा
सत्यमेव जयते
मुळशी-२
MULSHI - 2

[G. R., R. D., No. 10022/34 of 18-10-40]
[Do No. Desk-VI. 1582, dt. 4-7-86 Prom D. O. P. and S. Mumbai]

गाव नमुना सात (अधिकार अभिलेख पत्रक)

म. गा. २४ म.
R. V. 24 m.

[महाराष्ट्र जमीन महसूल अधिकार अभिलेख आणि नोंदवह्या (तयार करणे व सुस्थितीत ठेवणे) नियम, १९७१ यातील नियम ३, ५, ६ आणि ७]

गाव **भुगाव** तालुका **मुळशी**

भूमापन क्रमांक	भूमापन क्रमांकाचा उपविभाग	भूधारणा पद्धती
१४३	ची पुरवणी	नं. ३
शेताचे स्थानिक नाव		

लागवडीयोग्य क्षेत्र	हेक्टर	आर
.....		
.....		
.....		
एकूण		
पोटखराब (लागवडीयोग्य नसलेले)-		
वर्ग (अ) ..		
वर्ग (ब) ..		
एकूण ...		
	रुपये	पैसे
आकारणी ..		
जुडी किंवा विशेष आकारणी ...		

भोगवटादाराचे नाव
सारंग सुधाकर कोळे
रामेश सुधाकर कोळे
१ हे ५०.५९ आर
(६६६०)
श्रीमती बर्नडिट डायस
0-23.2 (५४१६)
0-23.20 (५४१७)

खाते क्रमांक
कुळाचे नाव खंड
रु. पै.
इतर अधिकार
सीमा आणि भूमापन चिन्हे

गाव नमुना बारा (पिकांची नोंदवही)

[महाराष्ट्र जमीन महसूल अधिकार अभिलेख आणि नोंदवह्या (तयार करणे व सुस्थितीत ठेवणे) नियम, १९७१ यातील नियम २१]

वर्ग	हंगाम	पिकाखालील क्षेत्रांचा तपशील									लागवडीसाठी उपलब्ध नसलेली जमीन		जल सिंचनाचे साधन	जमीन कसणाऱ्याचे नाव	शेरा
		मिश्र पिकाखालील क्षेत्र						निर्भेळ पिकाखालील क्षेत्र							
		पिकाचा संकेत क्रमांक	जल सिंचित	अजल सिंचित	घटक पिके व प्रत्येका-खालील क्षेत्र			जल सिंचित	अजल सिंचित		एकूण				
					पिकाचे नाव	जल सिंचित	अजल सिंचित	पिकाचे नाव							
१	२	३	४	५	६	७	८	९	१०	११	१२	१३	१४	१५	१६
			हे. आ.	हे. आ.		हे. आ.	हे. आ.		हे. आ.	हे. आ.		हे. आ.			

पुरवणी १+३ = ४ असे

दस्त क्रमांक: 2 3 [illegible] 2016

दुय्यम निबंधक
मौजे भुगांव ता. मुळशी, जि. पुणे
(सहदुय्यम नि. दे एस. एस.)

म ल स - २

२३६१ | ३८ | १४५

२०१६

THE SEAL OF THE SUB-REGISTRAR OF मुळशी

Do No. Desk-VI 1582, dt. 4-7-86 From D. G. P. ards S. Mumbai] गाव नमुना सात (अधिकार अभिलेख पत्रक) R. V. 24 m.

[महाराष्ट्र जमीन महसूल अधिकार अभिलेख आणि नोंदवह्या (तयार करणे व सुस्थितीत ठेवणे) नियम, १९७१ यातील नियम ३, ५, ६ आणि ७]

गाव **भुगाव** तालुका **मुळशी**

भूमापन क्रमांक	भूमापन क्रमांकाचा उपविभाग	भूधारणा पद्धती
१५०	3	भोगवटदार वर्ग १
शेताचे स्थानिक नाव	चौक	

लागवडीयोग्य क्षेत्र	हेक्टर	आर
.....	0	०६.१
.....		
.....		
एकूण	0	०६.१
पोटखराब (लागवडीयोग्य नसलेले)-		
वर्ग (अ) ..		
वर्ग (ब) ..		
एकूण ..	0	०६.१
आकारणी ..	रुपये	पैसे
जुडी किंवा विशेष आकारणी ..	0	४४

भोगवटादाराचे नाव

७ ५०५ ५१६० ५३६१ ५४६२

सारंग सुधाकर कोळे

राजेश सुधाकर कोळे

६६६०

खाते क्रमांक

कुळाचे नाव खंड रु. पै.

इतर अधिकार तुकडा

३२२५

सीमा आणि भूमापन चिन्हे

गाव नमुना बारा (पिकांची नोंदवही)

[महाराष्ट्र जमीन महसूल अधिकार अभिलेख आणि नोंदवह्या (तयार करणे व सुस्थितीत ठेवणे) नियम, १९७१ यातील नियम २९]

वर्ष	गाम	पिकाखालील क्षेत्रांचा तपशील									लागवडीसाठी उपलब्ध नसलेली जमीन		जल सिंचनाचे साधन	जमीन करणाऱ्याचे नाव	शेरा
		मिश्र पिकाखालील क्षेत्र					निर्भेळ पिकाखालील क्षेत्र								
		भूमापन क्रमांक	जल सिंचित	अजल सिंचित	घटक पिके व प्रत्येकाखालील क्षेत्र: पिकाचे नाव	जल सिंचित	अजल सिंचित	पिकाचे नाव	जल सिंचित	अजल सिंचित	खरब	क्षेत्र			
१	२	३	४	५	६	७	८	९	१०	११	१२	१३	१४	१५	१६
			हे. आ.	हे. आ.		हे. आ.	हे. आ.		हे. आ.	हे. आ.		हे. आ.			
२०१० २०११								भात ०.०६.१						खु.	
२०११ २०१२				—				भात ०.०६.१						खु.	
२०१२ २०१३								पड						खु.	
२०१३ २०१४								पड						खु.	

धनंजय तलाती

मुगांव, ता. मुळशी, जि. पुणे

तारीख: 23 JUN 2014 (श्रीपती. दिंडरे एस. एस.)

म ल स - २

१२३६१ | ३६ | १४५

२०१८

THE SEAL OF THE SUB-REGISTRAR OF मुख्य निबंधक मुळशी-२ यांची मुद्रा मुळशी-२ MULSHI - 2

[G. R., R. D., No. 10022/24 of 18-10-40]
[Do-No. Desk-VI-1582, dt. 4-7-86 From D. G. P. and S. Mumbai]

म. गा. २४ म.
R. V. 24 m.

गाव नमुना सात (अधिकार अभिलेख पत्रक)

[महाराष्ट्र जमीन महसूल अधिकार अभिलेख आणि नोंदवह्या (तयार करणे व सुस्थितीत ठेवणे) नियम, १९७१ यातील नियम ३, ५, ६ आणि ७]

गाव **भुगाव** तालुका **मुळशी**

भूमापन क्रमांक	भूमापन क्रमांकाचा उपविभाग	भूधारणा पद्धती
१५०	७	भोगवटादार वर्ग १

शेताचे स्थानिक नाव चौक

लागवडीयोग्य क्षेत्र	हेक्टर	आर
.....		
.....	०	०३·३
.....		
एकूण	०	०३·३
पोटखराब (लागवडीयोग्य नसलेले)-		
वर्ग (अ) ..		
वर्ग (ब) ..		
एकूण ..	०	०३·३
	रुपये	पैसे
आकारणी ..		
जुडी किंवा विशेष आकारणी ..	०	१६

भोगवटादाराचे नाव	खाते क्रमांक
रामभाऊ सोपाना शेडगे	कुळाचे नाव खंड रु. पै.
दामू सोपाना शेडगे	
इंदुमती बबन शेडगे	
मैनाबाई दिलीप जगताप	इतर अधिकार तुकडा
संजाबाई सोपान मारणे	१९४६ ३६६७ ५६६४ ६२०२
सावित्रा बबन शेडगे	
शिवाजी बबन शेडगे	
अ.पा.क. आई इंदुमती	
हरिभाऊ नामदेव शेडगे	
मनोहर नामदेव शेडगे	
अनुसयाबाई बाबूराव मोकाशी	
५०५ १३६० १७६२ १८४८ ६३०१	शेरा आणि भूमापन चिन्हे
३१३२ ३६६७	

पुढील पानावर पुरवणी पहा

गाव नमुना बारा (पिकांची नोंदवही)

[महाराष्ट्र जमीन महसूल अधिकार अभिलेख आणि नोंदवह्या (तयार करणे व सुस्थितीत ठेवणे) नियम, १९७१ यातील नियम २९]

वर्ष	हंगाम	पिकाखालील क्षेत्रांचा तपशील: मिश्र पिकाखालील क्षेत्र: मिश्रणाचा संकेत क्रमांक	मिश्र: जल सिंचित	मिश्र: अजल सिंचित	मिश्र: घटक पिके व प्रत्येकाखालील क्षेत्र: पिकाचे नाव	मिश्र: घटक पिके: जल सिंचित	मिश्र: घटक पिके: अजल सिंचित	निर्भेळ पिकाखालील क्षेत्र: पिकाचे नाव	निर्भेळ: जल सिंचित	निर्भेळ: अजल सिंचित	लागवडीसाठी उपलब्ध नसलेली जमीन: स्वरूप	लागवडीसाठी उपलब्ध नसलेली जमीन: क्षेत्र	जल सिंचनाचे साधन	जमीन करणाराचे नाव	शेरा
१	२	३	४	५	६	७	८	९	१०	११	१२	१३	१४	१५	१६
			हे. आ.	हे. आ.		हे. आ.	हे. आ.		हे. आ.	हे. आ.		हे. आ.			
२०१०/२०११								भात ०·०३·३						खु	
२०११/२०१२								भात ०·०३·३						खु	
२०१२/२०१३								भात ०·०३·३						खु	
२०१३/२०१४								भात ०·०३·३						खु	

पुढील पानावर पुरवणी पहा

म ल स - २

१२३६१ ४० १४५

Do No. Desk-VI/ 1582, dt. 4-7-86 From D. G. P. and S. Mumbai]

गाव नमुना सात (अधिकार अभिलेख पत्रक)

[महाराष्ट्र जमीन महसूल अधिकार अभिलेख आणि नोंदवह्या (तयार करणे व सुस्थितीत ठेवणे) नियम, १९७१ यातील नियम ३, ५ आणि ७]

गाव **भुगाव** तालुका **मुळशी**

भूमापन क्रमांक	भूमापन क्रमांकाचा उपविभाग	भूधारणा पद्धती
१५०	७ ची पुरवणी	नं. १

शेताचे स्थानिक नाव

लागवडीयोग्य क्षेत्र	हेक्टर	आर
.....		
.....		
.....		
एकूण		
पोटखराब (लागवडीयोग्य नसलेले)-		
वर्ग (अ) ..		
वर्ग (ब) ..		
एकूण ..		
	रुपये	पैसे
आकारणी ..		
जुडी किंवा विशेष आकारणी ..		

भोगवटादाराचे नाव

१) दत्तात्रय नारायण शेडगे
२) जयश्री संतोष दगडे
३) छाया मनोहर चौधरी
४) माया तुकाराम मते
५) विमल नारायण शेडगे

(६१४५)

सारंग सुधाकर काळे

क्षेत्र ०-०१।१ आर (६६६७)

+ ०-०१-१ (६३८)

दु.नं. १४।७।१४

खाते क्रमांक

कुळाचे नाव खंड

रु. पै.

इतर अधिकार

सीमा आणि भूमापन चिन्हे

गाव नमुना बारा (पिकांची नोंदवही)

[महाराष्ट्र जमीन महसूल अधिकार अभिलेख आणि नोंदवह्या (तयार करणे व सुस्थितीत ठेवणे) नियम, १९७१ यातील नियम २९]

वर्ष	हंगाम	पिकाखालील क्षेत्रांचा तपशील									लागवडीसाठी उपलब्ध नसलेली जमीन		जल सिंचनाचे साधन	जमीन करणाराचे नाव	शेरा
		मिश्रणाचा संकेत क्रमांक	मिश्र पिकाखालील क्षेत्र: जल सिंचित	मिश्र पिकाखालील क्षेत्र: अजल सिंचित	घटक पिके व प्रत्येकाखालील क्षेत्र: पिकाचे नाव	घटक पिके व प्रत्येकाखालील क्षेत्र: जल सिंचित	घटक पिके व प्रत्येकाखालील क्षेत्र: अजल सिंचित	निर्भेळ पिकाखालील क्षेत्र: पिकाचे नाव	निर्भेळ पिकाखालील क्षेत्र: जल सिंचित	निर्भेळ पिकाखालील क्षेत्र: अजल सिंचित	स्वरूप	क्षेत्र			
१	२	३	४	५	६	७	८	९	१०	११	१२	१३	१४	१५	१६
			हे. आ.	हे. आ.		हे. आ.	हे. आ.		हे. आ.	हे. आ.		हे. आ.			

पुरवणी १५७ ते 2

नकाशा तयार तारीख: १४।७।२०१४

कामगार तलाठी
भोजे भुगाव, ता. मुळशी, जि. पुणे
(श्रीमती. किंडरे एस. एल.)

म ल स - २

१२३८१ | ४१ | १४५

२०१६

THE SEAL OF THE SUB-REGISTRAR OF दुय्यम निबंधक मुळशी-२ यांची मुद्रा सत्यमेव जयते मुळशी-२ MULSHI - 2

[G. R. R. D. No. 10022/24 of 18-10-40]
Do No. Desk-VI 1582, dt. 4-7-86 From D. O. P. and S. Mumbai]

गाव नमुना सात (अधिकार अभिलेख पत्रक)

म. ना. २४ म.
R. V. 24 m.

[महाराष्ट्र जमीन महसूल अधिकार अभिलेख आणि नोंदवह्या (तयार करणे व सुस्थितीत ठेवणे) नियम, १९७१ यातील नियम ३, ५, ६ आणि ७]

गाव भुगाव तालुका मुळशी

भूमापन क्रमांक	भूमापन क्रमांकाचा उपविभाग	भूधारणा पद्धती
१५२	2	भोगवटादार वर्ग १

शेताचे स्थानिक नाव चौक

भोगवटादाराचे नाव
७ ५०० १७६२ १८३६ ४८६५ ५१६० ५४६२
सारंग सुधाकर काळे
रामेश सुधाकर काळे
६६६०

खाते क्रमांक
कुळाचे नाव खंड रु. पै.

इतर अधिकार तुकडा

लागवडीयोग्य क्षेत्र	हेक्टर	आर
.....	0	०८.६
.....		
.....		
एकूण	0	०८.६
पोटखराब (लागवडीयोग्य नसलेले)-		
वर्ग (अ) ..	0	02
वर्ग (ब) ..		
एकूण ..	0	१०.६
	रुपये	पैसे
आकारणी ..		
जुडी किंवा विशेष आकारणी ..	0	४७

सीमा आणि भूमापन चिन्हे

गाव नमुना बारा (पिकांची नोंदवही)

[महाराष्ट्र जमीन महसूल अधिकार अभिलेख आणि नोंदवह्या (तयार करणे व सुस्थितीत ठेवणे) नियम, १९७१ यातील नियम २९]

वर्ष	हंगाम	पिकाखालील क्षेत्रांचा तपशील: मिश्र पिकाखालील क्षेत्र: मिश्रणाचा संकेत क्रमांक	मिश्र: जल सिंचित	मिश्र: अजल सिंचित	मिश्र: घटक पिके व प्रत्येकाखालील क्षेत्र: पिकाचे नाव	मिश्र: जल सिंचित	मिश्र: अजल सिंचित	निर्भेळ पिकाखालील क्षेत्र: पिकाचे नाव	निर्भेळ: जल सिंचित	निर्भेळ: अजल सिंचित	लागवडीसाठी उपलब्ध नसलेली जमीन: स्वरूप	लागवडीसाठी उपलब्ध नसलेली जमीन: क्षेत्र	जल सिंचनाचे साधन	जमीन करणाऱ्याचे नाव	शेरा
१	२	३	४	५	६	७	८	९	१०	११	१२	१३	१४	१५	१६
			हे. आ.	हे. आ.		हे. आ.	हे. आ.		हे. आ.	हे. आ.		हे. आ.			
२०१० / २०११								भात ०.०८.६						खु.	
२०११ / २०१२								भात ०.०८.६						खु.	
२०१२ / २०१३								भात ०.०८.६						खु.	
२०१३ / २०१४								भात ०.०८.६						खु.	

तलाठी

मौजे भुगांव, ता. मुळशी, जि. पुणे

दिनांक 23 JUN 2014 (श्रीमती. किंडरे एस. एस.)

म ल स - २

~~१२९~~ १२३९ | ४२ १४५

THE SEAL OF THE SUB-REGISTRAR OF ASSURANCES मुळशी-२

Do No. Desk-VI [illegible] dt. 4-7-86 From D. G. P. and S. Mumbai]

गाव नमुना सात (अधिकार अभिलेख पत्रक)

R. V. 24 m.

[महाराष्ट्र जमीन महसूल अधिकार अभिलेख आणि नोंदवह्या (तयार करणे व सुस्थितीत ठेवणे) नियम, १९७१ यातील नियम ३, ५, ६ आणि ७]

गाव **भुगाव** तालुका **मुळशी**

भूमापन क्रमांक	भूमापन क्रमांकाचा उपविभाग	भूधारणा पद्धती
१५४	२	भोगवटादार वर्ग १

शेताचे स्थानिक नाव चोल

भोगवटादाराचे नाव: ५०९ १७९२ १९३९ ५१९० ५३९१ ५४१२

सारंग सुधाकर कोळे
राजेश सुधाकर कोळे
९९९०

लागवडीयोग्य क्षेत्र	हेक्टर	आर
.....	०	१४
.....		
.....		
एकूण	०	१४
खराब (लागवडीयोग्य नसलेले)-		
वर्ग (अ) ..		
वर्ग (ब) ..		
एकूण ..	०	१४
आकारणी ..	रुपये ०	पैसे १९
जुडी किंवा विशेष आकारणी ..		

खाते क्रमांक

कुळाचे नाव खंड रु: पै.

इतर अधिकार तुकडा

सीमा आणि भूमापन चिन्हे

गाव नमुना बारा (पिकांची नोंदवही)

[महाराष्ट्र जमीन महसूल अधिकार अभिलेख आणि नोंदवह्या (तयार करणे व सुस्थितीत ठेवणे) नियम, १९७१ यातील नियम २९]

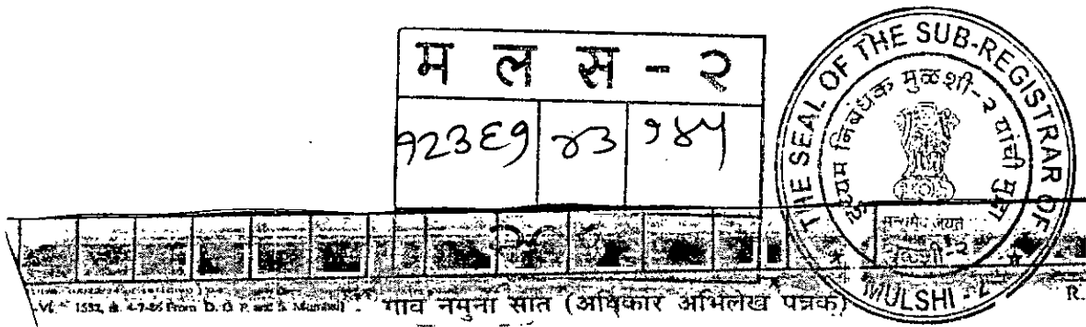
वर्ष	हंगाम	पिकाखालील क्षेत्रांचा तपशील								लागवडीसाठी उपलब्ध नसलेली जमीन		जल सिंचनाचे साधन	जमीन कसणाऱ्याचे नाव	शेरा
		मिश्र पिकाखालील क्षेत्र					निर्भेळ पिकाखालील क्षेत्र							
		भूमापन क्रमांक	जल सिंचित	अजल सिंचित	घटक पिके व प्रत्येकाखालील क्षेत्र: पिकाचे नाव	जल सिंचित	अजल सिंचित	पिकाचे नाव	जल सिंचित	अजल सिंचित	वर्ग	क्षेत्र			
१	२	३	४	५	६	७	८	९	१०	११	१२	१३	१४	१५	१६
			हे. आ.	हे. आ.		हे. आ.	हे. आ.		हे. आ.	हे. आ.		हे. आ.			
२०१०/२०११	रब्बी				भात ०.०७			भावत ०.०७						किसन पंडु शेडगे	
२०११/२०१२	खरीप				भात ०.०७			भावत ०.०७						सदर	
२०१२/२०१३	रब्बी				भात ०.०७			भावत ०.०७						सदर	
२०१३/२०१४	खरीप				भात ०.०७			भावत ०.०७						सदर	

तलाठी

मौजे भुगांव, ता. मुळशी, जि. पुणे
(श्रीमती. हिंडरे एस. एस.)

23 JUN 2014

म ल स - २		
२३६१	४३	१४५



V. C. 1552, d. 27-8-86 from D. O. P. and S. Mumbai. गाव नमुना सात (अधिकार अभिलेख पत्रक) R. V. 24 m.

[महाराष्ट्र जमीन महसूल अधिकार अभिलेख आणि नोंदवह्या (तयार करणे व सुस्थितीत ठेवणे) नियम, १९७१ यातील नियम ३, ५, ६ आणि ७]

गाव [illegible] तालुका मुळशी

भूमापन क्रमांक	भूमापन क्रमांकाचा उपविभाग	भूधारणा पद्धती
१५४	६	[illegible]

शेताचे स्थानिक नाव .....

लागवडीयोग्य क्षेत्र	हेक्टर	आर
.....		
.....	१	१७
.....		
एकूण	१	१७
पोटखराब (लागवडीयोग्य नसलेले)-		
वर्ग (अ) ..	०	०३
वर्ग (ब) ..		
एकूण ..	१	२०
	रुपये	पैसे
आकारणी ..	१	२५
जुडी किंवा विशेष आकारणी ..		

भोगवटादाराचे नाव
रामभाऊ सोपाना शेडगे
रामू सोपाना शेडगे
इंदुमती बबन शेडगे
मैनाबाई दिलीप सणस
संजाबाई सोपान मारणे
सावित्रा बबन शेडगे
शिवाजी बबन शेडगे
अ.पा.क. माई इंदुमती
हरिभाऊ नामदेव शेडगे
मनोहर नामदेव शेडगे
अनुसयाबाई बाबूराव मोकाशी
१०८ १३८० १७८२ १९४८ ३१३२ ६०१
३९६७
१) दत्तात्रय नारायण शेडगे
२) जयश्री संतोष दगडे

खाते क्रमांक
कुळाचे नाव. खंड
रु. पै.
.....

इतर अधिकार
१९४९ ३९६७ ५९९४ ६२०२

सीमा आणि भूमापन चिन्हे

पुढील पानावर पुरवणी पहा

गाव नमुना बारा (पिकांची नोंदवही)

[महाराष्ट्र जमीन महसूल अधिकार अभिलेख आणि नोंदवह्या (तयार करणे व सुस्थितीत ठेवणे) नियम, १९७१ यातील नियम २९]

सर्व	हंगाम	पिकाखालील क्षेत्रांचा तपशील									लागवडीसाठी उपलब्ध नसलेली जमीन		जल सिंचनाचे साधन	कमीन करणाऱ्याचे नाव	शेरा
		मिश्र पिकाखालील क्षेत्र						निर्भेळ पिकाखालील क्षेत्र							
					घटक पिके व प्रत्येकाखालील क्षेत्र										
		पिकाचा संकेतांक	जल सिंचित	अजल सिंचित	पिकाचे नाव	जल सिंचित	अजल सिंचित	पिकाचे नाव	जल सिंचित	अजल सिंचित	एकदर	क्षेत्र			
१	२	३	४	५	६	७	८	९	१०	११	१२	१३	१४	१५	१६
			हे. आ.	हे. आ.		हे. आ.	हे. आ.		हे. आ.	हे. आ.		हे. आ.			
२०१० / २०११	रब्बी						गवत १.१७							रघु	
२०११ / २०१२	खरीप						गवत १.१७							रघु	
२०१२ / २०१३	रब्बी						गवत १.१७							रघु	
२०१३ / २०१४	खरीप						गवत १.१०							रघु	

पुढील पानावर पुरवणी पहा

म ल स - २

१२३९/२०१४

२०१९

THE SEAL OF THE SUB-REGISTRAR OF मुळशी-२ MULSHI-2

G. R. R. D. No. 1082/2a of 18-10-49]
Do No Desk-VI - 1582, dt. 4-7-86 From D. G. P. and S, Mumbai]

गाव नमुना सात (अधिकार अभिलेख पत्रक)

दि. X 24 m.

[महाराष्ट्र जमीन महसूल अधिकार अभिलेख आणि नोंदवह्या (तयार करणे व सुस्थितीत ठेवणे) नियम, १९७१ यातील नियम ३, ५, ६ आणि ७]

गाव भुगाव तालुका मुळशी

भूमापन क्रमांक	भूमापन क्रमांकाचा उपविभाग	भूधारणा पद्धती
१५४	६ ची पुरवणी	नं. १
शेताचे स्थानिक नाव		

लागवडीयोग्य क्षेत्र	हेक्टर	आर
.....		
.....		
.....		
एकूण		
पोटखराब (लागवडीयोग्य नसलेले)-		
वर्ग (अ) ..		
वर्ग (ब) ..		
एकूण ..		
आकारणी ..	रुपये	पैसे
जुडी किंवा विशेष आकारणी ...		

भोगवटादाराचे नाव

३) छाया मनोहर चौधरी
४) माया तुकाराम मते
५) विमल नारायण शेडगे

(६१४५)

सारंग सुधाकर जाधव
क्षेत्र 0-40 आर (६६५५)
+ 1 हे 40 आर
(६३०१) हुकुम
१४/७/१४

खाते क्रमांक

कुळाचे नाव खंड
रु. पै.

इतर अधिकार

सीमा आणि भूमापन चिन्हे

गाव नमुना बारा (पिकांची नोंदवही)

[महाराष्ट्र जमीन महसूल अधिकार अभिलेख आणि नोंदवह्या (तयार करणे व सुस्थितीत ठेवणे) नियम, १९७१ यातील नियम २९]

वर्ष	हंगाम	पिकाखालील क्षेत्रांचा तपशील									लागवडीसाठी उपलब्ध नसलेली जमीन		जल सिंचनाचे साधन	जमीन करणाराचे नाव	शेरा
		मिश्र पिकाखालील क्षेत्र						निर्भेळ पिकाखालील क्षेत्र							
		मिश्रणाचा संकेत क्रमांक	जल सिंचित	अजल सिंचित	घटक पिके व प्रत्येकाखालील क्षेत्र: पिकाचे नाव	जल सिंचित	अजल सिंचित	पिकाचे नाव	जल सिंचित	अजल सिंचित	स्वरूप	क्षेत्र			
१	२	३	४	५	६	७	८	९	१०	११	१२	१३	१४	१५	१६
			हे. आ.	हे. आ.		हे. आ.	हे. आ.		हे. आ.	हे. आ.		हे. आ.			

भुगाव १+ १ ब. = अखे

तयार केल्याचा तारीख: १४/७/२०१४

कारकून सर्कल
मौजे भुगाव, ता. मुळशी, जि. पुणे
(भीमाशी शिंदे एम. एल.)

म ल स - २
१२३९१	४५	१४५
२०१६

THE SEAL OF THE SUB-REGISTRAR OF मुळशी-२ MULSHI-2

R. V. 24 m.

Do No. Desk-VI 1582, dt. 4-7-86 From D. G. P. and S. Mumbai]

गाव नमुना सात (अधिकार-अभिलेख पत्रक)

[महाराष्ट्र जमीन महसूल अधिकार अभिलेख आणि नोंदवह्या (तयार करणे व सुस्थितीत ठेवणे) नियम, १९७१ यातील नियम ३, ५, ६ आणि ७]

गाव **भुगाव** तालुका **मुळशी**

भूमापन क्रमांक	भूमापन क्रमांकाचा उपविभाग	भूधारणा पद्धती
१५५	४	भोगवटदार वर्ग १

शेताचे स्थानिक नाव ३५०

लागवडीयोग्य क्षेत्र	हेक्टर	आर
.....		
.....		
.....	०=	०९.८
एकूण	०=	०९.८
पोटखराब (लागवडीयोग्य नसलेले)-		
वर्ग (अ) ..	०=	०२.३
वर्ग (ब) ..		
एकूण ..	०=	१२.१
	रुपये	पैसे
आकारणी ..	०=	६६
जुडी किंवा विशेष आकारणी ..		

भोगवटादाराचे नाव

हरिभाऊ नामदेव शेडगे
मनोहर नामदेव शेडगे
रामभाऊ सोपान शेडगे
दामु सोपान शेडगे
इंदुबाई सोपान शेडगे
मैनाबाई दिलीप सणस
संजाबाई सोपान मारणे
सावित्रा बबन शेडगे
शिवाजी बबन शेडगे
अ.पा.क. आई इंदुबाई
अनुसयाबाई बाबूराव मोकाशी
३५३ ५१० ७१२ १३८० १९४८ ६२०१
१९४९ ३९६७
१) दत्तात्रय नारायण शेडगे
२) जाधी संतोष दगडे

खाते क्रमांक

कुळाचे नाव खंड

रु. पै.

इतर अधिकार तुकडा

१९४९ ३३५३ ३९६७ ५४०३ ५९९४ ६२०२

सीमा आणि भूमापन चिन्हे

पुढील पानावर पुरवणी पहा

गाव नमुना बारा (पिकांची नोंदवही)

[महाराष्ट्र जमीन महसूल अधिकार अभिलेख आणि नोंदवह्या (तयार करणे व सुस्थितीत ठेवणे) नियम, १९७१ यातील नियम २९]

वर्ष	हंगाम	पिकाखालील क्षेत्रांचा तपशील: मिश्र पिकाखालील क्षेत्र: पिकाचा संकेत क्रमांक	मिश्र पिकाखालील क्षेत्र: जल सिंचित	मिश्र पिकाखालील क्षेत्र: अजल सिंचित	घटक पिके व प्रत्येकाखालील क्षेत्र: पिकाचे नाव	घटक पिके व प्रत्येकाखालील क्षेत्र: जल सिंचित	घटक पिके व प्रत्येकाखालील क्षेत्र: अजल सिंचित	निर्भेळ पिकाखालील क्षेत्र: पिकाचे नाव	निर्भेळ पिकाखालील क्षेत्र: जल सिंचित	निर्भेळ पिकाखालील क्षेत्र: अजल सिंचित	लागवडीसाठी उपलब्ध नसलेली जमीन: स्वरूप	लागवडीसाठी उपलब्ध नसलेली जमीन: क्षेत्र	जल सिंचनाचे साधन	जमीन करणाऱ्याचे नाव	शेरा
१	२	३	४	५	६	७	८	९	१०	११	१२	१३	१४	१५	१६
			हे. आ.	हे. आ.		हे. आ.	हे. आ.		हे. आ.	हे. आ.		हे. आ.			
२०१०/२०११	ख					भात ०=०९.८								खु.	
२०११/२०१२	अ				भात ०=९८									खु	
२०१२/२०१३	ख				भात ०=०९.८									खु	
२०१३/२०१४	अ				भात ०=०९.८									खु	

पुढील पानावर पुरवणी पहा

म ल स - २

THE SEAL OF THE SUB-REGISTRAR OF मुळशी-२ MULSHI-2

D. R., P. T., No. 10022/24 of 18-10-40]
Do No. Desk-VI. 1582, dt. 4-7-86 From D. G. P. attl S. Mumbai]

गाव नमुना सात (अधिकार अभिलेख पत्रक) ★ मुळशी-२ ★ R. V. 24 m.

[महाराष्ट्र जमीन महसूल अधिकार अभिलेख आणि नोंदवह्या (तयार करणे व सुस्थितीत ठेवणे) नियम, १९७१ यातील नियम ३, ५ आणि ७]

गाव **भुगाव** तालुका **मुळशी**

भूमापन क्रमांक	भूमापन क्रमांकाचा उपविभाग	भूधारणा पद्धती
१५५	४-ची पुरवणी नं. १	

शेताचे स्थानिक नाव

लागवडीयोग्य क्षेत्र	हेक्टर	आर
.....		
.....		
.....		
एकूण		
पोटखराब (लागवडीयोग्य नसलेले)-		
वर्ग (अ) ..		
वर्ग (ब) ..		
एकूण ..		

आकारणी ..	रुपये	पैसे
जुडी किंवा विशेष आकारणी		

भोगवटादाराचे नाव
३) ढाया मनोहर चौधरी
४) माया तुकाराम मते
५) विमल नारायण शेडगे
(६१४५)
सारंग सुधाकर काळे
क्षेत्र ०-०४।०३ आर
(६६६७)
+ ०हे ०४।०३ आर दु.नि. २४/७/१४
(६३०१)

खाते क्रमांक
कुळाचे नाव खंड
रु. पै.
इतर अधिकार
सीमा आणि भूमापन चिन्हे

गाव नमुना बारा (पिकांची नोंदवही)

[महाराष्ट्र जमीन महसूल अधिकार अभिलेख आणि नोंदवह्या (तयार करणे व सुस्थितीत ठेवणे) नियम, १९७१ यातील नियम २९]

वर्ष	हंगाम	पिकाखालील क्षेत्रांचा तपशील									लागवडीसाठी उपलब्ध नसलेली जमीन		जल सिंचनाचे साधन	जमीन करणाऱ्याचे नाव	शेरा
		मिश्र पिकाखालील क्षेत्र			घटक पिके व प्रत्येका-खालील क्षेत्र			निर्भेळ पिकाखालील क्षेत्र							
		मिश्रणाचा संकेत क्रमांक	जल सिंचित	अजल सिंचित	पिकाचे नाव	जल सिंचित	अजल सिंचित	पिकाचे नाव	जल सिंचित	अजल सिंचित	स्वरूप	क्षेत्र			
१	२	३	४	५	६	७	८	९	१०	११	१२	१३	१४	१५	१६
			हे. आ.	हे. आ.		हे. आ.	हे. आ.		हे. आ.	हे. आ.		हे. आ.			

पुरवणी १+१ = २ करणे

तलाठी तयार तारीख: १४/७/२०१४

कामगार तलाठी
मौजे भुगांव, ता. मुळशी, जि. पुणे
(श्रीमती. किंजरे एस. एस.)

म ल स - २

१२३६१	४७	१४५

२०१६

THE SEAL OF THE SUB-REGISTRAR OF दि. उपनिबंधक मुळशी-२ यांची मुद्रा सत्यमेव जयते मुळशी-२ MULSHI-2

गाव नमुना सात (अधिकार अभिलेख पत्रक)

[महाराष्ट्र जमीन महसूल अधिकार अभिलेख आणि नोंदवहया (तयार करणे व सुस्थितीत ठेवणे) नियम, १९७१ यातील नियम ३, ५, ६ आणि ७]

गाव भुगाव तालुका मुळशी

भूमापन क्रमांक	भूमापन क्रमांकाचा उपविभाग	भूधारणा पद्धती
१५५	६	वर्ग एक

शेताचे स्थानिक नाव चौक

लागवडीयोग्य क्षेत्र	हेक्टर	आर
.....		
.....		
.....	०	१०.१
एकूण	०	१०.१
पोटखराब (लागवडीयोग्य नसलेले)-		
वर्ग (अ) ..	०	०१
वर्ग (ब) ..		
एकूण ..	०	११.१

आकारणी / जुडी किंवा विशेष आकारणी	रुपये	पैसे
	०	६६

भोगवटादाराचे नाव

हरिभाऊ नामदेव शेडगे
मनोहर नामदेव शेडगे
रामभाऊ सोपान शेडगे
रामु सोपान शेडगे
इंदुबाई सोपान शेडगे
मैनाबाई दिलीप सणस
संजाबाई सोपान भारेण
सावित्रा बबन शेडगे
शिवाजी बबन शेडगे
अ.पा.क. आई इंदुबाई
अनुसयाबाई बाबुराव मोकाशी
५१० १३८० १७६२ १९४८ ६३०१
३८६७
१) दत्तात्रय नारायण शेडगे
२) जयश्री संतोष दगडे

खाते क्रमांक
कुळाचे नाव खंड
रु. पै.

इतर अधिकार तुकडा
मधुबाई धोंडीबा चोंधे
१९४६ ३८६७ ५४०३
अशोक पुरुषोत्तम परकुंडे
रेजना चंद्रकांत दोडके
५९९४ ६८१६

सीमा आणि भूमापन चिन्हे

गाव नमुना बारा (पिकांची नोंदवही) पुढील पानावर पुरवणी पहा.

[महाराष्ट्र जमीन महसूल अधिकार अभिलेख आणि नोंदवहया (तयार करणे व सुस्थितीत ठेवणे) नियम, १९७१ यातील नियम २९]

वर्ष	हंगाम	पिकाखालील क्षेत्रांचा तपशील: मिश्र पिकाखालील क्षेत्र: मिश्रणाचा संकेत क्रमांक	मिश्र: जल सिंचित	मिश्र: अजल सिंचित	मिश्र: घटक पिके व प्रत्येकाखालील क्षेत्र: पिकाचे नाव	मिश्र: जल सिंचित	मिश्र: अजल सिंचित	निर्भेळ पिकाखालील क्षेत्र: पिकाचे नाव	निर्भेळ: जल सिंचित	निर्भेळ: अजल सिंचित	लागवडीसाठी उपलब्ध नसलेली जमीन: क्षेत्रफळ	लागवडीसाठी उपलब्ध नसलेली जमीन: शेरा	जल सिंचनाचे साधन	जमीन कसणाऱ्याचे नाव	शेरा
१	२	३	४	५	६	७	८	९	१०	११	१२	१३	१४	१५	१६
			हे. आ.	हे. आ.		हे. आ.	हे. आ.		हे. आ.	हे. आ.		हे. आ.			
२०१०/२०११	ख						भात ०-१०.१							खु.	
२०११/२०१२	ख						भात ०-१०.१							खु.	
२०१२/२०१३	ख						भात ०-१०.१							खु.	
२०१३/२०१४	ख						भात ०-१०.१							खु.	

पुढील पानावर पुरवणी पहा